國土測繪圖資服務雲
介接服務技術手冊

中 華 民 國 113 年 11 月 01 日

目錄

第一章 WFS 服務與範例 1

第一節 WFS 服務介紹 1

第二節 WFS 使用範例 8

第二章 API 服務 19

第一節 門牌 API 服務 19

第二節 地籍圖 API 服務 31

第三節 地籍 API 服務 36

第四節 國土利用 API 服務 53

第五節 路徑規劃 API 服務 58

第六節 開放 API 服務 64

第七節 圖臺 API 服務 88

第一章 WFS服務與範例

第一節 WFS服務介紹

一、WFS 介接說明

(一) WFS URL

https://wfs.nlsc.gov.tw/WFS

(二) WFS 傳入參數說明

編碼：UTF-8

參數	說明
SERVICE=WFS	服務種類
VERSION=1.0.0	請求的 WFS 服務版本
REQUEST=GetFeature	請求的 WFS 操作
OUTPUTFORMAT	輸出格式(GML)
SRSNAME	指定回傳圖徵的空間參考系統（EPSG 4326, 3826, 3825）
TYPENAME	指定圖層名稱
FILTER	Filter 描述如何對圖徵進行操作，取代 BBOX
BBOX	指定包圍矩形，取代 FILTER

(三) 支援 WFS 2.0

同時支援 WFS 1.0 及 WFS 2.0，只需在介接時的設定改為 2.0，以下圖 QGIS 為例：

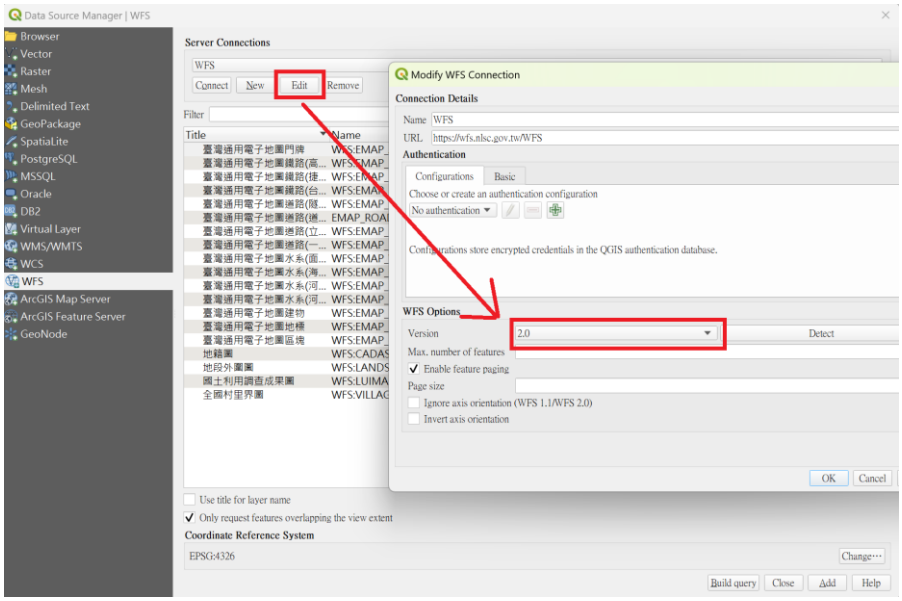

另外傳送參數與回傳的 XML 內容有差異，以下說明：

1. GetCapabilities 差異

Request URL 與 回傳 XML 內容不同

(1) WFS 2.0

http://wfs.nlsc.gov.tw/S_WFS/WFS?SERVICE=WFS&REQUEST=GetCapabilities&VERSION=2.0.0

(2) WFS 1.0

http://wfs.nlsc.gov.tw/S_WFS/WFS?SERVICE=WFS&REQUEST=GetCapabilities&VERSION=1.0.0

2. GetFeature 差異

	WFS 1.0 GetFeature	WFS 2.0 GetFeature
圖層參數名稱	TYPENAME	TYPENAMES
Filter 參數名稱	PropertyName	ValueReference
範例	http://wfs.nlsc.gov.tw/S_WFS/WFS?SERVICE=WFS&REQUEST=GetFeature&VERSION=1.0.0&TYPENAME=WFS:TOPO01K_112_BUILD&MAXFEATURES=1000&SRSNAME=EPSG:4326&FILTER=<ogc:Filter xmlns:gml="http://www.opengis.net/gml" xmlns:ogc="http://www.opengis.net/ogc"> <ogc:And> <ogc:BBOX> <ogc:PropertyName>MultiSurfacePropertyType </ogc:PropertyName> <gml:Box srsName="EPSG:4326"> <gml:coordinates ts="" cs=",">120.82699999999999818,24.25159999999999982 120.83299999999999841,24.25369999999999848</gml:coordinates> </gml:Box> </ogc:BBOX> <ogc:And xmlns:ogc="http://www.opengis.net/ogc"> <ogc:PropertyIsEqualTo xmlns:ogc="http://www.opengis.net/ogc">	http:// wfs.nlsc.gov.tw /S_WFS/WFS?SERVICE=WFS&REQUEST=GetFeature&VERSION=2.0.2&TYPENAMES=WFS:TOPO01K_112_BUILD&SRSNAME=EPSG:4326&FILTER=<fes:Filter xmlns:gml="http://www.opengis.net/gml/3.2" xmlns:fes="http://www.opengis.net/fes/2.0"> <fes:And> <fes:BBOX> <fes:ValueReference>MultiSurfacePropertyType</fes:ValueReference> <gml:Envelope srsName="EPSG:4326"> <gml:lowerCorner>24.25159999999999982 120.82699999999999818</gml:lowerCorner> <gml:upperCorner>24.25369999999999848 120.83299999999999841</gml:upperCorner> </gml:Envelope> </fes:BBOX> <fes:And xmlns:fes="http://www.opengis.net/fes/2.0"> <fes:PropertyIsEqualTo xmlns:fes="http://www.opengis.net/fes/2.0"> <fes:ValueReference>point</fes:ValueReference>

	<ogc:PropertyName xmlns:ogc="http://www.opengis.net/ogc">point </ogc:PropertyName> <ogc:Literal xmlns:ogc="http://www.opengis.net/ogc">120.830093,24.252705</ogc:Literal> </ogc:PropertyIsEqualTo> <ogc:PropertyIsEqualTo xmlns:ogc="http://www.opengis.net/ogc"> <ogc:PropertyName xmlns:ogc="http://www.opengis.net/ogc">distance</ogc:PropertyName> <ogc:Literal xmlns:ogc="http://www.opengis.net/ogc">100</ogc:Literal> </ogc:PropertyIsEqualTo> </ogc:And> </ogc:And> </ogc:Filter>	<fes:Literal xmlns:fes="http://www.opengis.net/fes/2.0">120.830093,24.252705</fes:Literal> </fes:PropertyIsEqualTo> <fes:PropertyIsEqualTo xmlns:fes="http://www.opengis.net/fes/2.0"> <fes:ValueReference>distance</fes:ValueReference> <fes:Literal xmlns:fes="http://www.opengis.net/fes/2.0">100</fes:Literal> </fes:PropertyIsEqualTo> </fes:And> </fes:And> </fes:Filter>

二、WFS 圖層列表

類別(圖層名稱)	圖層代碼	型態	輸出屬性欄位	備註
臺灣通用電子地圖道路(道路中線)	EMAP_ROAD	線	道路線段識別碼,道路等級編碼 1,道路等級編碼 2,公路編碼,縣市名稱,鄉鎮市區名稱,道路結構碼,道路編號,道路編號 1,道路編號 2,道路名稱,道路別名,共線路段數,段名,橋梁名隧道名,巷名,弄名,路寬,起節點識別碼,迄節點識別碼,測製年月,資料建置代碼,來源定義代碼,方向性代碼	
臺灣通用電子地圖道路(一般道路)	EMAP_ROADA	面	多邊形序號	
臺灣通用電子地圖道路(立體道路)	EMAP_HROADA	面	多邊形序號	
臺灣通用電子地圖道路(隧道)	EMAP_TUNNELA	面	多邊形序號	
臺灣通用電子地圖鐵路(台鐵)	EMAP_RAIL	線	臺灣鐵路線段識別碼,臺灣鐵路線段名稱,臺灣鐵路類型代碼,測製年月,來源定義代碼	
臺灣通用電子地圖鐵路(高鐵)	EMAP_HSRAIL	線	高速鐵路線段識別碼, 高速鐵路線段名稱高速鐵路類型代碼,測製年月,來源	

			定義代碼	
臺灣通用電子地圖鐵路(捷運)	EMAP_RT	線	捷運線段識別碼,捷運系統名稱,捷運線段名稱,捷運類型代碼,測製年月,來源定義代碼	
臺灣通用電子地圖水系(河川)	EMAP_RIVERA	面	多邊形序號	
臺灣通用電子地圖水系(河川中線)	EMAP_RIVERL	線	河川線段識別碼,河川類型代碼,河川等級,河川名稱,測製年月,資料建置代碼,來源定義代碼	
臺灣通用電子地圖水系(面狀水域)	EMAP_WATERA	面	面狀水域識別碼,面狀水域類型代碼,面狀水域名稱,測製年月,資料建置代碼,來源定義代碼	
臺灣通用電子地圖水系(海岸線)	EMAP_ COASTLINE	線	線段序號,測製年月,資料建置代碼	
臺灣通用電子地圖區塊	EMAP_BLOCK	面	多邊形序號,區塊分類代碼(1 學校/2 博物館美術館文化中心/3 公園植物園動物園/4 體育場體育館/5 室外停車場/6 醫院),區塊名稱,測製年月	
臺灣通用電子地圖建物	EMAP_BUILD	面	多邊形序號,測製年月,資料建置代碼	
臺灣通用電子地圖地標	EMAP_MARK	點	地標識別碼,地標分類代碼 1(政府機關及單位、文教機關及場所、醫療社福	

			及殯葬設施、公共及紀念場所、生活機能設施及機構、交通運輸設施及其他等 7 類),地標分類代碼 2,地標名稱,地標簡稱,測製年月,地址,電話	
臺灣通用電子地圖門牌	EMAP_ADDRESS	點	門牌資料點序號,門牌資料點識別碼,鄉鎮市區名稱,村里名,鄰名,路街道名,段名,地區名,巷名,弄名,衖名,衕名,門牌號碼,TWD97 坐標系統 E 坐標值,TWD97 坐標系統 N 坐標值,地址	
地籍圖	CADAS_MERGE	面	縣市、地段、地號、鄉鎮市區、地所、面積、使用分區、用地編定、公告地價、公告現值。	
國土利用調查成果圖	LUIMAP	面	一級分類代碼(Lcode_C1)、二級分類代碼(Lcode_C2)、三級分類代碼(Lcode_C3)	
全國村里界圖	VILLAGE_NLSC	面	直轄市縣市 ID、鄉鎮市區 ID、村里 ID、直轄市縣市(C_Name)、鄉鎮市區(T_Name)、村里(V_Name)	註 1

第二節　WFS 使用範例

一、點查詢

(一) 使用 GET

Request
https://wfs.nlsc.gov.tw/WFS?SERVICE=WFS&VERSION=1.0.0&REQUEST=GetFeature&TYPENAME=**WFS:village_nlsc**&SRSNAME=**EPSG4326**&outputFormat="GML"&FILTER=<ogc:Filter xmlns:ogc="https://www.opengis.net/ogc"><ogc:PropertyIsEqualTo><ogc:PropertyName>point</ogc:PropertyName><ogc:Literal>**120.630656,24.150840**</ogc:Literal></ogc:PropertyIsEqualTo></ogc:Filter>
Response
向量 GML (XML)

(二) 使用 QGIS

Request：QGIS 查詢表示式
’"point" =’120.630656,24.150840’
Response
向量 GML（ XML ）

二、矩框查詢

(一) 使用 GET

Request
https://wfs.nlsc.gov.tw/WFS?SERVICE=WFS&VERSION=1.0.0&REQUEST=GetFeature&TYPENAME=**WFS:emap_build**&SRSNAME=**EPSG3826**&outputFormat="GML"&FILTER=<ogc:Filter>xmlns:ogc="https://www.opengis.net/ogc"><ogc:PropertyIsEqualTo><ogc:PropertyName>box</ogc:PropertyName><ogc:Literal>**212466.106,2671777.886 213224.095,2672316.928**</ogc:Literal></ogc:PropertyIsEqualTo></ogc:Filter>
Response
向量 GML (XML)

(二) 使用 QGIS

Request：QGIS 查詢表示式
"box" ='212466.106,2671777.886 213224.095,2672316.928'
Response
向量 GML (XML)

三、圓查詢

(一) 使用 GET

Request
https://wfs.nlsc.gov.tw/WFS?SERVICE=WFS&VERSION=1.0.0&REQUEST=GetFeature&TYPENAME=**WFS:luimap**&SRSNAME=**EPSG4326**&outputFormat="GML"&FILTER=<ogc:Filter xmlns:ogc="https://www.opengis.net/ogc"><ogc:And><ogc:Prope

rtyIsEqualTo><ogc:PropertyName>point</ogc:PropertyName><ogc:Literal>**120.634413,24.153263**</ogc:Literal></ogc:PropertyIsEqualTo><ogc:PropertyIsEqualTo><ogc:PropertyName>distance</ogc:PropertyName><ogc:Literal>**200**</ogc:Literal></ogc:PropertyIsEqualTo></ogc:And></ogc:Filter>
Response
向量 GML (XML)

(二) 使用 QGIS

Request：QGIS 查詢表示式
"point" ='120.634413,24.153263' and "distance" ='200'
Response
向量 GML (XML)

四、多邊形查詢

(一) 使用 GET

Request
https://wfs.nlsc.gov.tw/WFS?SERVICE=WFS&VERSION=1.0.0&REQUEST=GetFeature&TYPENAME=**WFS:CADAS_MERGE**&SRSNAME=**EPSG4326**&outputFormat="GML"&FILTER=<ogc:Filter xmlns:ogc="https://www.opengis.net/ogc"><ogc:PropertyIsEqualTo><ogc:PropertyName>polygon</ogc:PropertyName><ogc:Literal>**120.637341,24.151219 120.632309,24.151189 120.634315,24.154714**</ogc:Literal></ogc:PropertyIsEqualTo></ogc:Filter>
Response
向量 GML (XML)

(二) 使用 QGIS

Request：QGIS 查詢表示式
"polygon" ='120.637341,24.151219 120.632309,24.151189 120.634315,24.154714'
Response
向量 GML (XML)

五、使用 GET 套疊 WFS 圖資說明

(一) 將 Request 的 url 貼到瀏覽器，會回傳 GML 向量 GML (XML)。

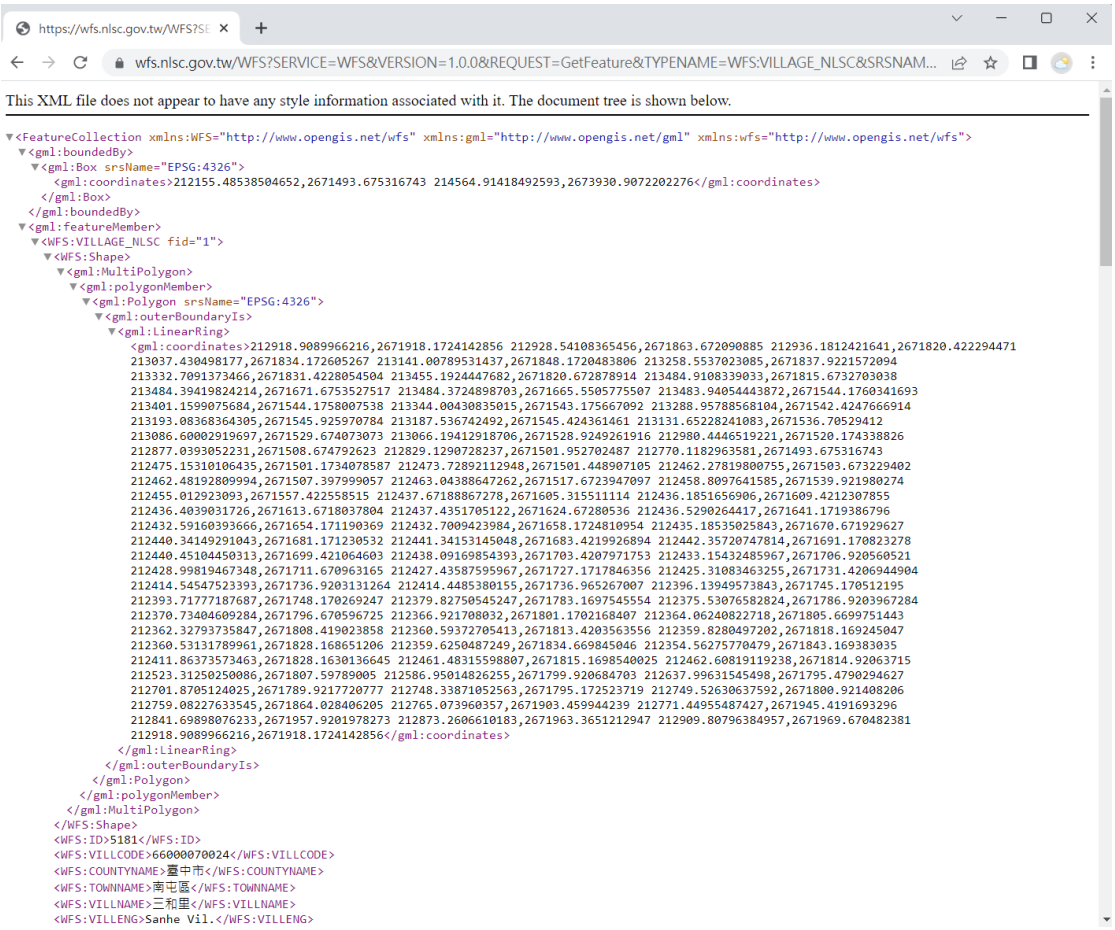


```
▼<FeatureCollection xmlns:WFS="http://www.opengis.net/wfs" xmlns:gml="http://www.opengis.net/gml" xmlns:wfs="http://www.opengis.net/wfs">
  ▼<gml:boundedBy>
    ▼<gml:Box srsName="EPSG:4326">
       <gml:coordinates>212155.48538504652,2671493.675316743 214564.91418492593,2673930.9072202276</gml:coordinates>
     </gml:Box>
   </gml:boundedBy>
  ▼<gml:featureMember>
    ▼<WFS:VILLAGE_NLSC fid="1">
      ▼<WFS:Shape>
        ▼<gml:MultiPolygon>
          ▼<gml:polygonMember>
            ▼<gml:Polygon srsName="EPSG:4326">
              ▼<gml:outerBoundaryIs>
                ▼<gml:LinearRing>
                   <gml:coordinates>212918.9089966216,2671918.1724142856 212928.54108365456,2671863.672090885 212936.1812421641,2671820.422294471
                   213037.430498177,2671834.172605267 213141.00789531437,2671848.1720483806 213258.5537023085,2671837.9221572094
                   213332.7091373466,2671831.4228054504 213455.1924447682,2671820.672878914 213484.9108339033,2671815.6732703038
                   213484.39419824214,2671671.6753527517 213484.3724898703,2671665.5505775507 213483.94054443872,2671544.1760341693
                   213401.1599075684,2671544.1758007538 213344.00430835015,2671543.175667092 213288.95788568104,2671542.4247666914
                   213193.08368364305,2671545.925970784 213187.536742492,2671545.424361461 213131.65228241083,2671536.70529412
                   213086.60002919697,2671529.674073073 213066.19412918706,2671528.9249261916 212980.4446519221,2671520.174338826
                   212877.0393052231,2671508.674792623 212829.1290728237,2671501.952702487 212770.1182963581,2671493.675316743
                   212475.15310106435,2671501.1734078587 212473.72892112948,2671501.448907105 212462.27819800755,2671503.673229402
                   212462.48192809994,2671507.397999057 212463.04388647262,2671517.6723947097 212458.8097641585,2671539.921980274
                   212455.012923093,2671557.422558515 212437.67188867278,2671605.315511114 212436.1851656906,2671609.4212307855
                   212436.4039031726,2671613.6718037804 212437.4351705122,2671624.67280536 212436.5290264417,2671641.1719386796
                   212432.59160393666,2671654.171190369 212432.7009423984,2671658.1724810954 212435.18535025843,2671670.671929627
                   212440.34149291043,2671681.171230532 212441.34153145048,2671683.4219926894 212442.35720747814,2671691.170823278
                   212440.45104450313,2671699.421064603 212438.09169854393,2671703.4207971753 212433.15432485967,2671706.920560521
                   212428.99819467348,2671711.670963165 212427.43587595967,2671727.1717846356 212425.31083463255,2671731.4206944904
                   212414.54547523393,2671736.9203131264 212414.4485380155,2671736.965267007 212396.13949573843,2671745.170512195
                   212393.71777187687,2671748.170269247 212379.82750545247,2671783.1697545554 212375.53076582824,2671786.9203967284
                   212370.73404609284,2671796.670596725 212366.921708032,2671801.1702168407 212364.06240822718,2671805.6699751443
                   212362.32793735847,2671808.419023858 212360.59372705413,2671813.4203563556 212359.8280497202,2671818.169245047
                   212360.53131789961,2671828.168651206 212359.6250487249,2671834.669845046 212354.56275770479,2671843.169383035
                   212411.86373573463,2671828.1630136645 212461.48315598807,2671815.1698540025 212462.60819119238,2671814.92063715
                   212523.31250250086,2671807.59789005 212586.95014826255,2671799.920684703 212637.99631545498,2671795.4790294627
                   212701.8705124025,2671789.9217720777 212748.33871052563,2671795.172523719 212749.52630637592,2671800.921408206
                   212759.08227633545,2671864.028406205 212765.073960357,2671903.459944239 212771.44955487427,2671945.4191693296
                   212841.69898076233,2671957.9201978273 212873.2606610183,2671963.3651212947 212909.80796384957,2671969.670482381
                   212918.9089966216,2671918.1724142856</gml:coordinates>
                 </gml:LinearRing>
               </gml:outerBoundaryIs>
             </gml:Polygon>
           </gml:polygonMember>
         </gml:MultiPolygon>
       </WFS:Shape>
       <WFS:ID>5181</WFS:ID>
       <WFS:VILLCODE>66000070024</WFS:VILLCODE>
       <WFS:COUNTYNAME>臺中市</WFS:COUNTYNAME>
       <WFS:TOWNNAME>南屯區</WFS:TOWNNAME>
       <WFS:VILLNAME>三和里</WFS:VILLNAME>
       <WFS:VILLENG>Sanhe Vil.</WFS:VILLENG>
```


(二) 滑鼠右鍵另存新檔，存成 xml 格式。

(三) 開啟 QGIS，套疊時選擇加入向量圖層(Vector Layer)

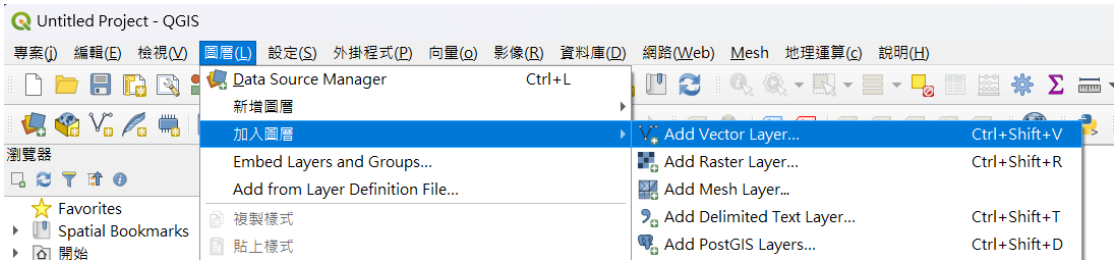

(四) 選取下載的 xml 檔，按下加入，即可顯示。

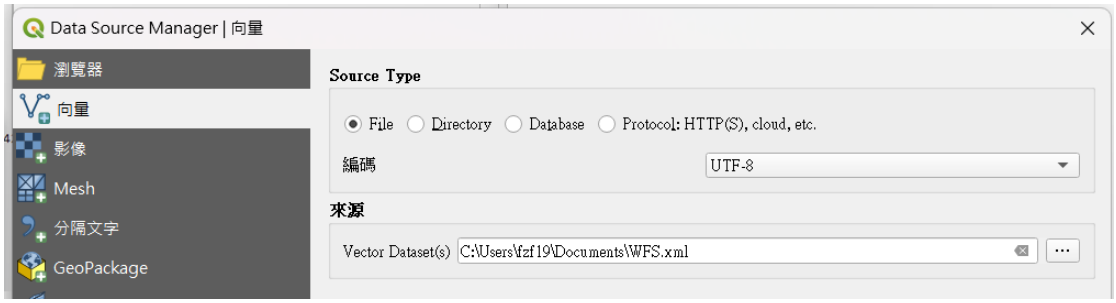

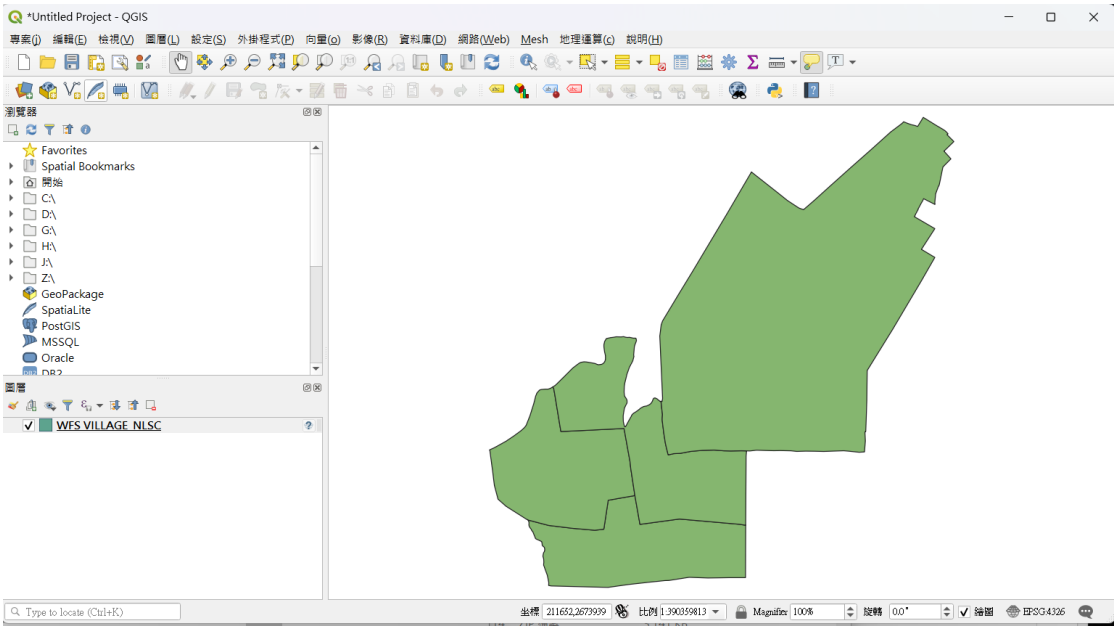

六、使用 QGIS 介接 WFS 說明(QGIS 3.X.X 版以上適用)

(一) 加入 WFS 圖層

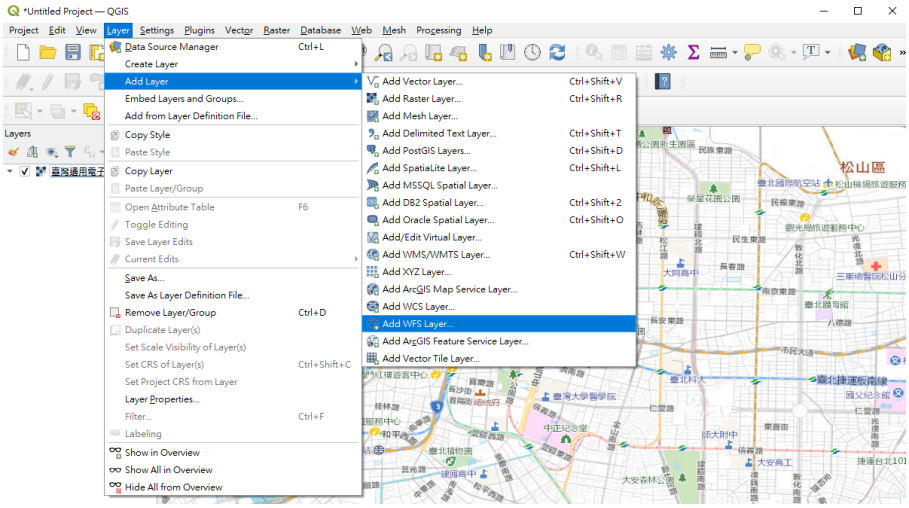

(二) 新增圖層，連結設定請填入 https://wfs.nlsc.gov.tw/WFS

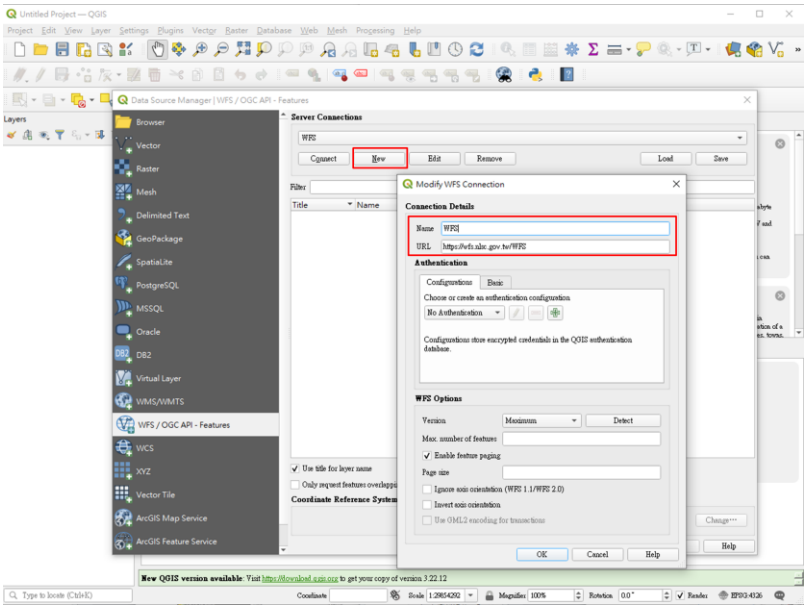

(三) 按下連接載入 WFS 圖資列表(僅全國村里界圖可免申請)，選擇要套疊的圖層，例如：全國村里界圖，按下「加入(Add)」

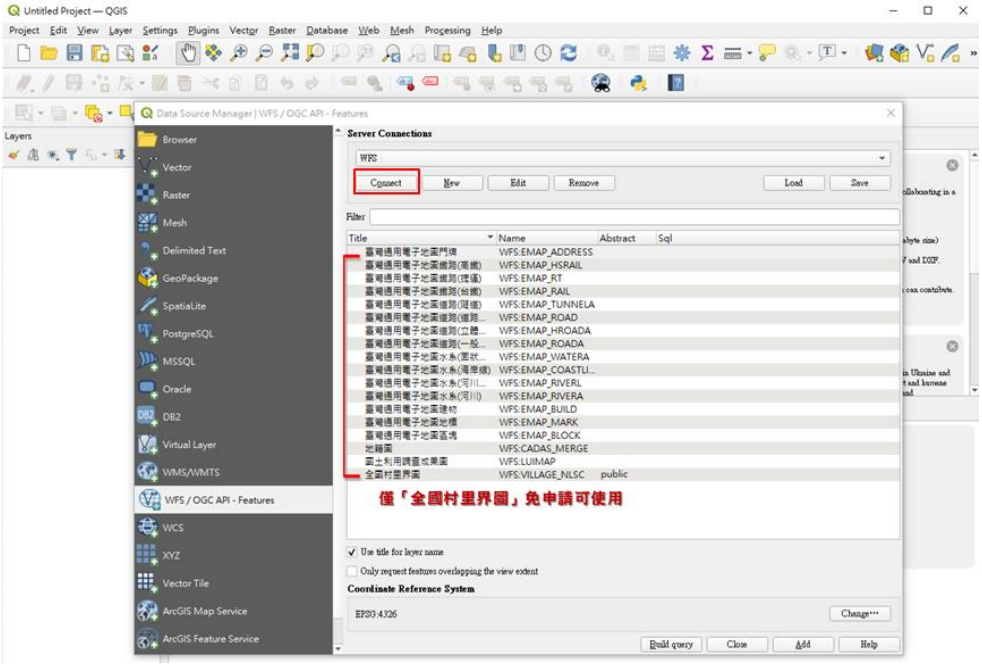

(四) 於圖層視窗，點全國村里界圖，按滑鼠右鍵→Filter→輸入查詢條件

示範矩框查詢("box" ='121.510392,25.039033 121.519764,25.042717')

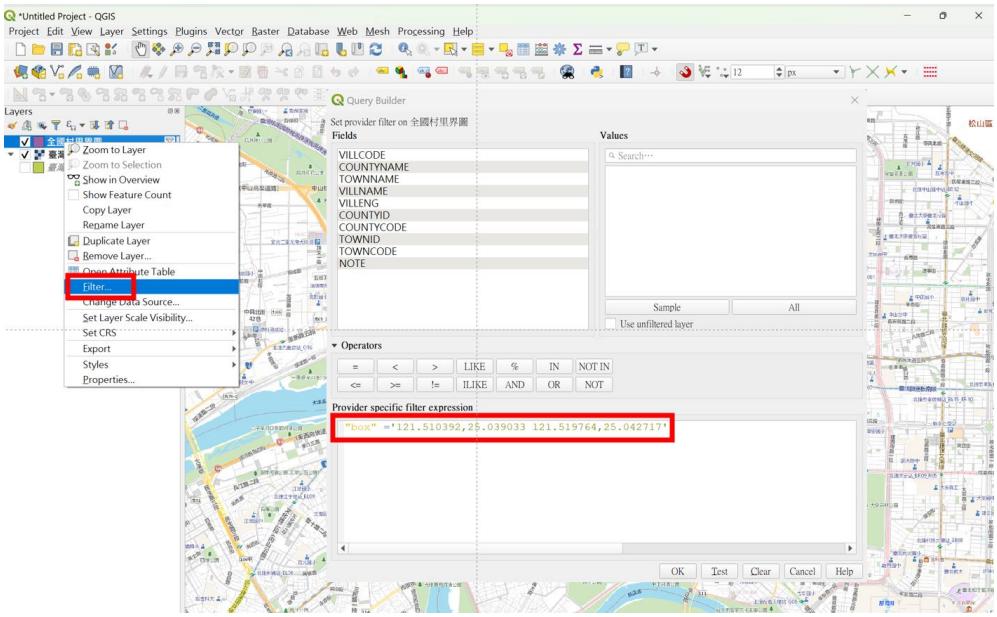

(五) 載入查詢結果並可與電子地圖套疊

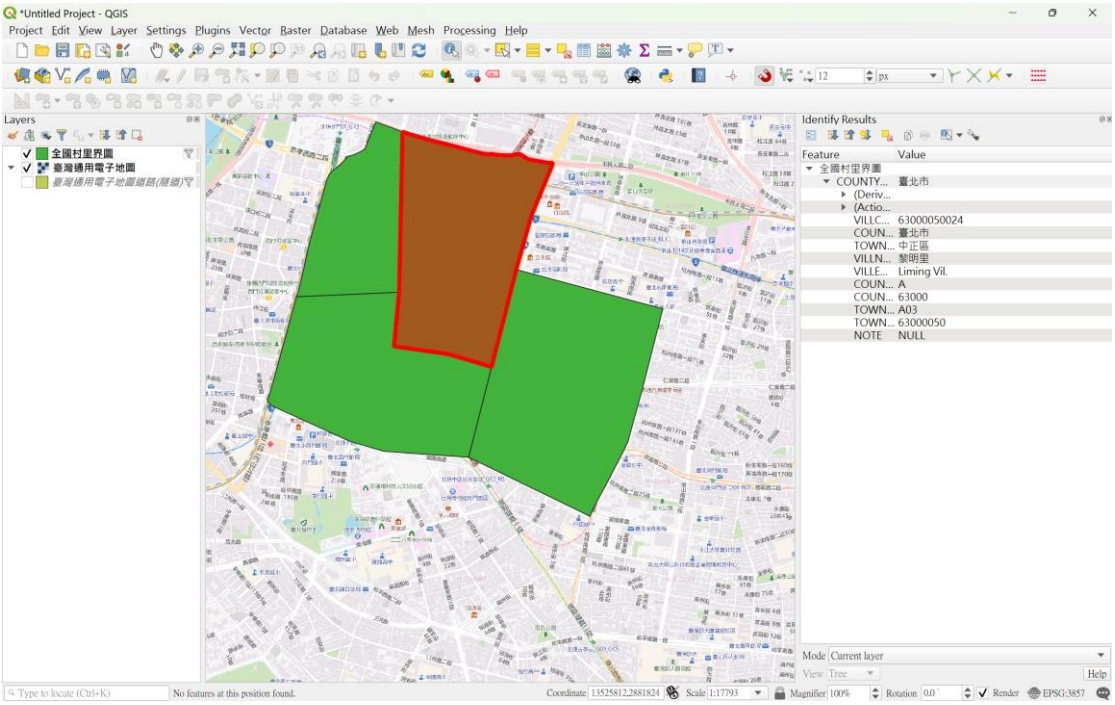

(六) 支援用屬性篩選查詢

以下用「臺灣通用電子地圖區塊」圖層為例，在圖層加入後，點「臺灣通用電子地圖區塊」，按滑鼠右鍵→Filter→輸入查詢條件"point" ='120.830093,24.252705' and "distance" ='500'，得到下圖結果。

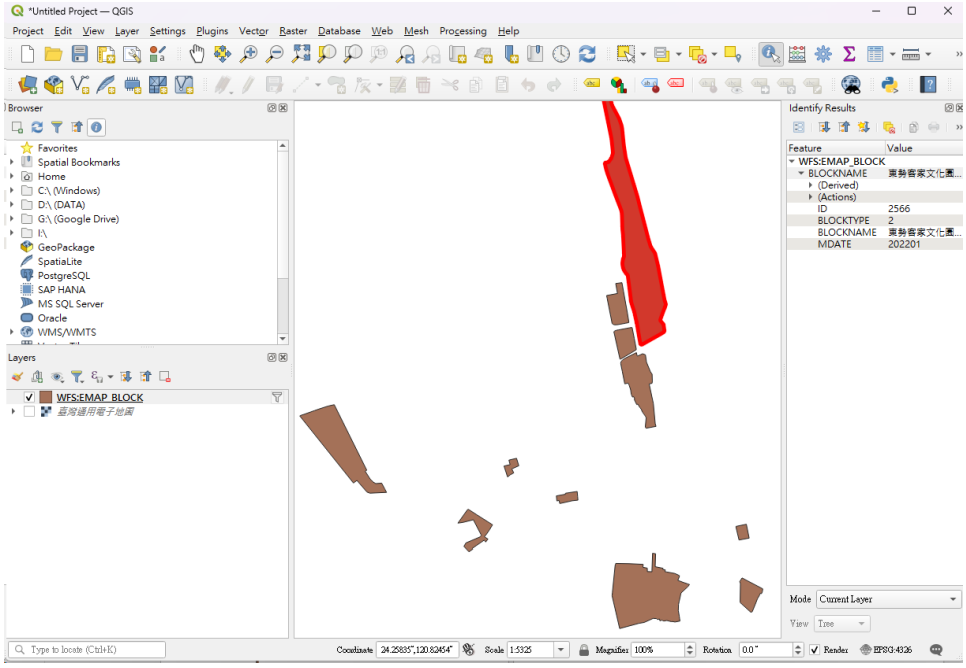

此時可進一步依屬性進行篩選，如篩選 BLOCKTYPE 為 5，Filter 的條件輸入「"BLOCKTYPE" = '5' and "point" ='120.830093,24.252705' and "distance" ='500'」，如下圖。

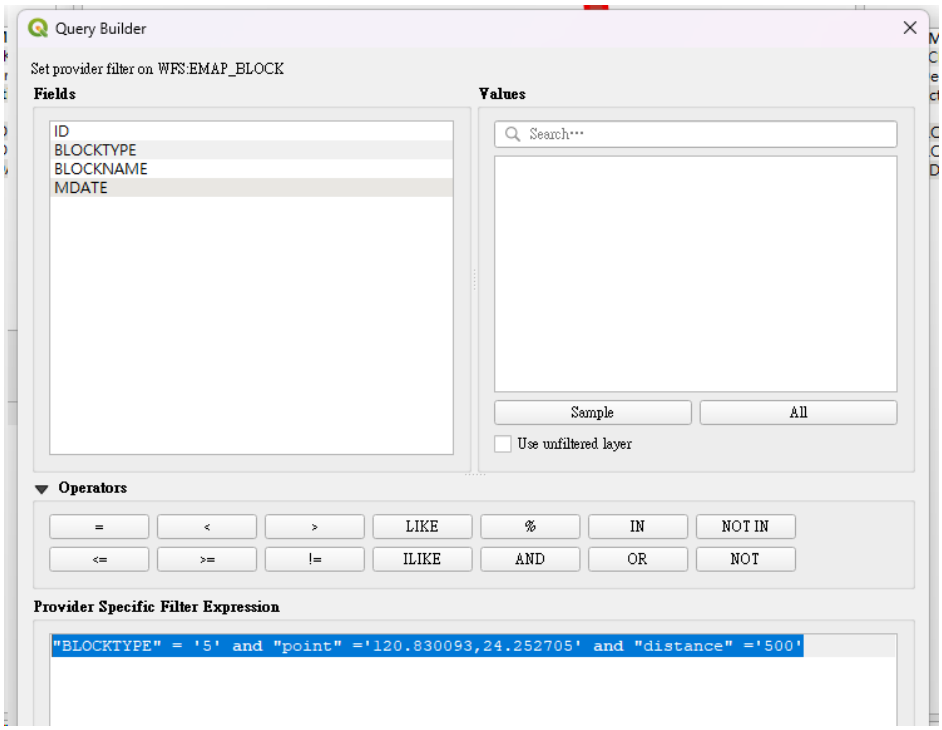

得到結果如下圖，成功篩選，僅顯示符合條件的圖資。

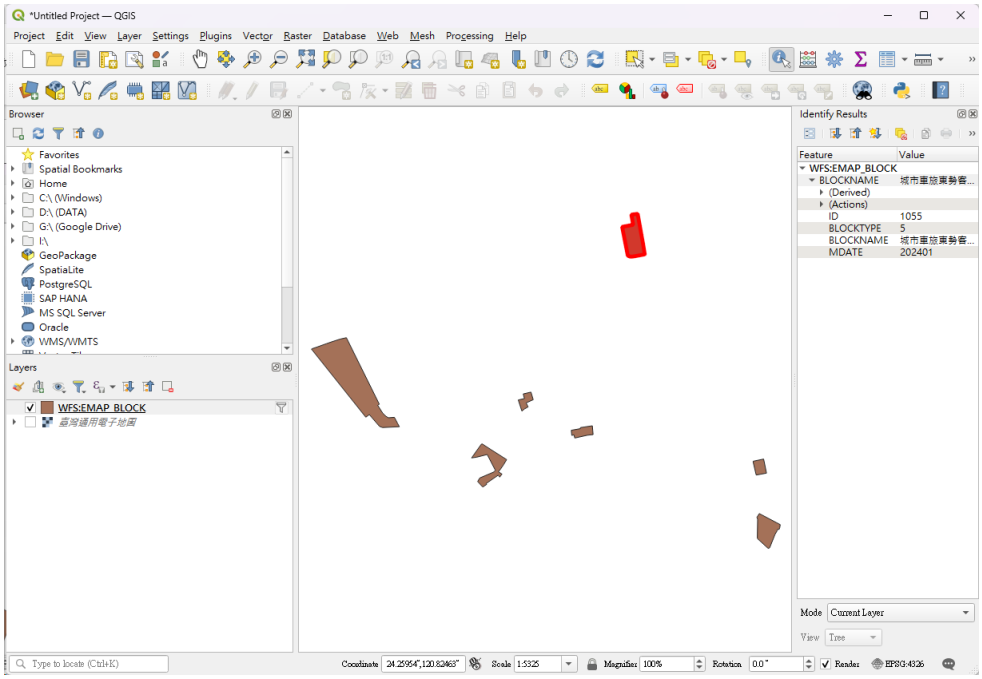

七、使用 QGIS 介接 WFS 說明(QGIS 2.X.X 版適用)

(一) 連結設定請填入 https://wfs.nlsc.gov.tw/WFS

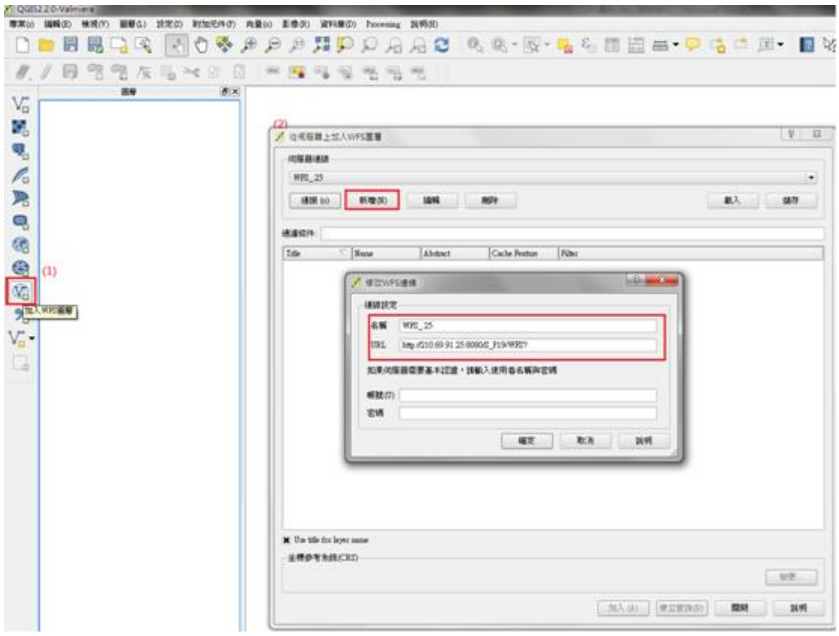

(二) 連接後選取任一圖層→建立查詢→利用「欄位與值」的內容，組出 filter，如下圖。

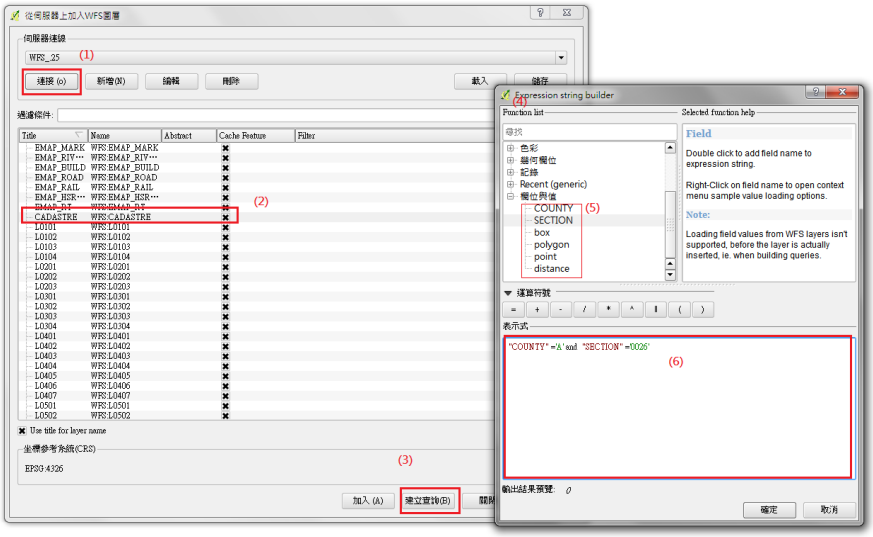

(三) 查詢參數請參考前述「WFS 使用範例」之說明。點選「加入」，即可取得資料，回傳結果顯示如下圖（示範指定矩框回傳結果），會自動縮放至回傳的資料範圍。

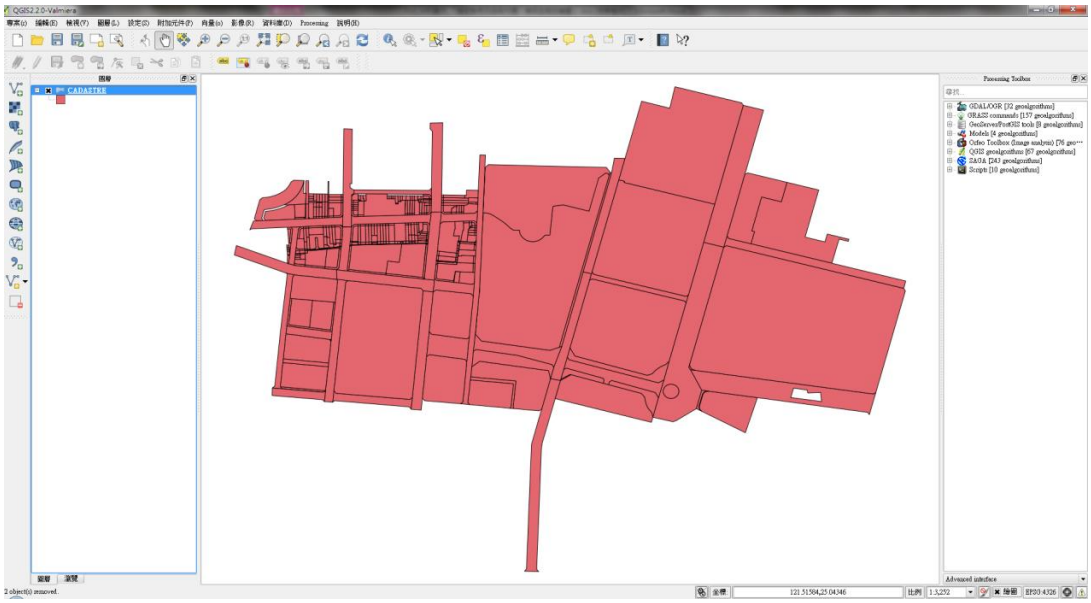

第二章 API 服務

第一節 門牌 API 服務

一、全文檢索

(一) URL

https://api.nlsc.gov.tw/idc/TextQueryMap/

URI	HTTP Method
/TextQueryMap/{搜尋字串}	GET
/TextQueryMap/{搜尋字串}/{回傳數量}	GET
/TextQueryMap/{搜尋字串}/{回傳數量}/{x 坐標}/{y 坐標}	GET
/TextQueryMap/{搜尋字串}/{回傳數量}/{縣市代碼}	GET

(二) 傳入參數說明

編碼：UTF-8

輸入參數	預設值	說明
{搜尋字串}		要進行檢索的字串
{回傳數量}	10	選取檢索結果最接近的筆數 (最大 25 筆)
{x 坐標}		參考點 X 坐標(經緯度)
{y 坐標}		參考點 Y 坐標(經緯度)
{縣市代碼}		縣市代碼 A~Z

(三) 回傳格式：application/xml

編碼：UTF-8

Parent Node	Node	Value
<ITEM>	<CONTENT>	完整名稱字串
	<KEY>	鍵值字串
	<LOCATION>	圖資位置(經緯度)
	<REMARK>	中文說明

(四) 範例

Request
https://api.nlsc.gov.tw/idc/TextQueryMap/文心/20/B/
Response


```
<?xml version="1.0" encoding="UTF-8" standalone="no"?>
<root>
  <ITEM>
    <CONTENT>玉山商業銀行文心分行，玉山銀行文心分行</CONTENT>
    <KEY>B,LANDGOAL,459</KEY>
    <LOCATION>120.6699,24.1738</LOCATION>
    <REMARK>地標, 定位坐標 :東經=120-40-12 秒北緯=24-10-26 秒</R
EMARK>
  </ITEM>
  <ITEM>
    <CONTENT>台塑石化福懋文心路加油站，福懋文心路站</CONTENT>
    <KEY>B,LANDGOAL,735</KEY>
    <LOCATION>120.6858,24.1724</LOCATION>
...
  </root>
```


二、門牌服務－全文檢索

(一) URL

https://api.nlsc.gov.tw/idc/TextQueryAddress/

URI	HTTP Method
/TextQueryAddress/{搜尋字串}/	GET

/TextQueryAddress/{搜尋字串}/{回傳數量}/	GET
/TextQueryAddress/{搜尋字串}/{回傳數量}/{縣市代碼}	GET

(二) 傳入參數說明

編碼：UTF-8

輸入參數	預設值	說明
{搜尋字串}		要進行檢索的字串
{回傳數量}	10	選取檢索結果最接近的筆數 (最大 25 筆)
{縣市代碼}		縣市代碼 A~Z

(三) 回傳格式：application/xml

編碼：UTF-8

Parent Node	Node	Value
<addressItem>	<content>	門牌
	<location>	位置(經緯度)

(四) 範例

Request
https://api.nlsc.gov.tw/idc/TextQueryAddress/黎明路/10/B/
Response
<?xml version="1.0" encoding="UTF-8" standalone="yes"?> <addressItems> <addressItem> <content>臺中市南屯區黎明里００１鄰黎明路二段４９７號</content> <location>120.63442,24.15341</location> </addressItem> … </addressItems>

三、門牌服務－路名清單

(一) URL

https://api.nlsc.gov.tw/idc/ListRoad/

URI	HTTP Method
/ListRoad/{縣市代碼}/{鄉鎮市區代碼}	GET

(二) 傳入參數說明

編碼：UTF-8

輸入參數	預設值	說明
{縣市代碼}		縣市代碼 A~Z
{鄉鎮市區代碼}		鄉鎮市區 3 碼

(三) 回傳格式：application/xml

編碼：UTF-8

Parent Node	Node	Value
<road>	<name>	路名

(四) 範例

Request
https://api.nlsc.gov.tw/idc/ListRoad/B/B04/
Response
<?xml version="1.0" encoding="UTF-8" standalone="yes"?> <roads> <road> <name>三民西路</name> </road> … </roads>

四、門牌服務－巷弄清單

(一) URL

https://api.nlsc.gov.tw/idc/ListRoadLaneAlley/

URI	HTTP Method
/ListRoadLaneAlley/{縣市代碼}/{鄉鎮市區代碼}/{道路名稱}	GET

(二) 傳入參數說明

編碼：UTF-8

輸入參數	預設值	說明
{縣市代碼}		縣市代碼 A~Z
{鄉鎮市區代碼}		鄉鎮市區 3 碼
{道路名稱}		道路名稱

(三) 回傳格式：application/xml

編碼：UTF-8

Parent Node	Node	Value
<laneAlleyItem>	<lane>	巷名
	<alleys>	弄名

(四) 範例

Request
https://api.nlsc.gov.tw/idc/ListRoadLaneAlley/B/B07/向心路/
Response
<?xml version="1.0" encoding="UTF-8" standalone="yes"?> <laneAlleyItems> <laneAlleyItem> <lane>１１５</lane> <alleys>１</alleys> <alleys>２</alleys> <alleys>３</alleys> <alleys>４</alleys>

```
    <alleys> 5 </alleys>
  </laneAlleyItem>
  …
</laneAlleyItems>
```


五、門牌服務－坐標回傳門牌服務（點坐標）

(一) URL

https://api.nlsc.gov.tw/idc/PointQueryAddr?

URI	HTTP Method
oPX={點坐標}&oPY={點坐標}&oBuffer={搜尋範圍}	POST
oPX={點坐標}&oPY={點坐標}&oBuffer={搜尋範圍}&oSRS={坐標系統}	POST
oPX={點坐標}&oPY={點坐標}&oBuffer={搜尋範圍}&oSRS={坐標系統}& oResultDataType ={資料格式}	POST

(二) 傳入參數說明

編碼：UTF-8

輸入參數	預設值	說明
{點坐標 X(oPX)}		必填，橫坐標
{點坐標 Y(oPY)}		必填，縱坐標
{搜尋範圍(oBuffer)}		必填，以上述點位向外延伸半徑距離，以公尺為計算單位
{坐標系統(oSRS)}	EPSG4326	EPSG4326 (WGS84) EPSG3825 (TWD97/TM2 Zone119) EPSG3826 (TWD97/TM2 Zone121)
{資料格式(oResultDataType)}	GeoJSON	GeoJSON JSON XML

(三) 回傳格式：application/ GEOJSON(預設)、JSON、XML；門牌

編碼：UTF-8

代碼	說明
coordinates	根據坐標系統，顯示對應的橫坐標（X）及縱坐標（Y）
FULL_ADDR	完整戶政門牌（包含縣市、鄉鎮市區、路名及門牌號）

(四) 範例

Request
https://api.nlsc.gov.tw/idc/PointQueryAddr?oPX=121.514073&oPY=25.061741&oBuffer=50
Response


```
{
  "type": "FeatureCollection",
  "features": [
    {
      "geometry": {
        "type": "Point",
        "coordinates": [
          121.514262,
          25.061771
        ]
      },
      "type": "Feature",
      "properties": {
        "FULL_ADDR": "臺北市大同區民權里４鄰蘭州街１之１號"
      }
    },
    {
      "geometry": {
        "type": "Point",
        "coordinates": [
          121.513983,
          25.061896
        ]
      },
      "type": "Feature",
```

```
        "properties": {
          "FULL_ADDR": "臺北市大同區民權里２鄰蘭州街４之１號"
        }
      }
    ]
}
```


六、門牌服務－坐標回傳門牌服務（線坐標）

(一) URL

https://api.nlsc.gov.tw/idc/LineQueryAddr?

URI	HTTP Method
oLineXY_List={坐標集合}&oBuffer={搜尋範圍}	POST
oLineXY_List={坐標集合}&oBuffer={搜尋範圍}&oSRS={坐標系統}	POST
oLineXY_List={坐標集合}&oBuffer={搜尋範圍}&oSRS={坐標系統}& oResultDataType ={資料格式}	POST

(二) 傳入參數說明

編碼：UTF-8

輸入參數	預設值	說明
{坐標集合(oLineXY_List)		必填，由兩組以上的橫縱坐標（X 坐標 Y 坐標）組成，各組坐標間以透點隔開
{搜尋範圍(oBuffer)}		必填，以上述範圍向外延伸距離，以公尺為計算單位
{坐標系統(oSRS)}	EPSG4326	EPSG4326 (WGS84) EPSG3825 (TWD97/TM2 Zone119) EPSG3826 (TWD97/TM2 Zone121)

{資料格式 (oResultDataType)}	GeoJSON	GeoJSON JSON XML

(三) 回傳格式：application/ GEOJSON(預設)、JSON、XML；門牌

編碼：UTF-8

代碼	說明
coordinates	根據坐標系統，顯示對應的橫坐標（X）及縱坐標（Y）
FULL_ADDR	完整戶政門牌（包含縣市、鄉鎮市區、路名及門牌號）

(四) 範例

Request
https://api.nlsc.gov.tw/idc/LineQueryAddr?oLineXY_List=121.513676 25.061826,121.514073 25.061741,121.514314 25.060832,121.513638&oBuffer=100
Response


```
{
  "type": "FeatureCollection",
  "features": [
    {
      "geometry": {
        "type": "Point",
        "coordinates": [
          121.514336,
          25.061146
        ]
      },
      "type": "Feature",
      "properties": {
        "FULL_ADDR": "臺北市大同區民權里４鄰寧夏路１４９號"
      }
    },
 …
}
```

七、門牌服務－坐標回傳門牌服務（面坐標）

(五) URL

https://api.nlsc.gov.tw/idc/PolygonQueryAddr?

URI	HTTP Method
oPolygonXY_List={坐標集合}&oBuffer={搜尋範圍}	POST
oPolygonXY_List={坐標集合}&oBuffer={搜尋範圍}&oSRS={坐標系統}	POST
oPolygonXY_List={坐標集合}&oBuffer={搜尋範圍}&oSRS={坐標系統}& oResultDataType ={資料格式}	POST

(六) 傳入參數說明

編碼：UTF-8

輸入參數	預設值	說明
{坐標集合(oPolygonXY_List)		必填，由三組以上的橫縱坐標（X 坐標 Y 坐標）組成，各組坐標間以透點隔開，如：x1 y1,x2 y2, ...xn yn
{搜尋範圍(oBuffer)}		必填，以上述範圍向外延伸距離，以公尺為計算單位
{坐標系統(oSRS)}	EPSG4326	EPSG4326 (WGS84) EPSG3825 (TWD97/TM2 Zone119) EPSG3826 (TWD97/TM2 Zone121)
{資料格式(oResultDataType)}	GeoJSON	GeoJSON JSON XML

(七) 回傳格式：application/ GEOJSON(預設)、JSON、XML；門

牌

編碼：UTF-8

代碼	說明
SRS	坐標系統
Buffer	搜尋範圍
Total	資料筆數
FULL_ADDR	完整戶政門牌（包含縣市、鄉鎮市區、路名及門牌號）
X	X 坐標
Y	Y 坐標

(八) 範例

Request
https://api.nlsc.gov.tw/idc/PolygonQueryAddr?oPolygonXY_List=121.513676 25.061826,121.514073 25.061741,121.514314 25.060832&oBuffer=10&oSRS=EPSG:4326&oResultDataType=json
Response

{
"Info": [
{
"SRS": "EPSG:4326",
"Buffer": "10.0",
"Total": "12"
}
],
"AddressList": [
{
"FULL_ADDR": "臺北市大同區民權里１１鄰涼州街８之１號",
"X": 121.513862,
"Y": 25.060732
},
{
"FULL_ADDR": "臺北市大同區民權里１１鄰涼州街６之１號",
"X": 121.514025,
"Y": 25.06074
}

```
  ]
}
```

第二節 地籍圖 API 服務

一、指定地號查詢地籍圖

(一) URL

https://api.nlsc.gov.tw/dmaps/CadasMapQuery/

URI	HTTP Method
/CadasMapQuery/{縣市代碼}/{地段代碼}	GET
/CadasMapQuery/{縣市代碼}/{地段代碼}/{地號}	GET
/CadasMapQuery/{縣市代碼}/{地段代碼}/{地號}/{檔案格式}	GET
/CadasMapQuery/{縣市代碼}/{地段代碼}/{地號}/{檔案格式}/{結果坐標系}	GET

(二) 傳入參數說明

編碼：UTF-8

輸入參數	預設值	說明
{縣市代碼}		必填，以英文 1 碼表示，由 A~Z 組成，例如：A=臺北市
{地段代碼}		必填，數字 4 碼
{地號}		必填，數字 8 碼
{檔案格式}	GML	gml, kml, shp
{結果坐標系}	EPSG4326	EPSG4326 (WGS84) EPSG3825 (TWD97/TM2 Zone119(澎湖)) EPSG3826 (TWD97/TM2 Zone121(臺灣))

(三) 回傳格式：GML(預設)、KML、SHP

編碼：UTF-8

參照 GML(Geography Markup Language)、KML（Keyhole Markup Language）、SHP（ESRI Shapefile）格式。

(四) 範例

Request
https://api.nlsc.gov.tw/dmaps/CadasMapQuery/B/0008/00010000
Response


```
<?xml version="1.0" encoding="UTF-8" standalone="no"?>
<FeatureCollection xmlns:WFS="https://www.opengis.net/wfs" xmlns:gml=
"https://www.opengis.net/gml" xmlns:wfs="https://www.opengis.net/wfs">
  <gml:boundedBy>
    <gml:Box srsName="EPSG:4326">
      <gml:coordinates>120.62233034812029,24.143183158452384
                       120.62252638897715,24.14335805281596
      </gml:coordinates>
    </gml:Box>
  </gml:boundedBy>
  <gml:featureMember>
    <WFS:CADASTRE fid="1">
      <WFS:Shape>
        <gml:MultiPolygon>
          <gml:polygonMember>
            <gml:Polygon srsName="EPSG:4326">
              <gml:outerBoundaryIs>
                <gml:LinearRing>
                  <gml:coordinates>120.6224901020486,24.1431831584
```

52384
120.62252638897715,24.14321801909702 120.622381241623,24.144334512944957 120.6223657018164 5,24.14335805281596 120.6223303 4812029,24.143324261629285120.6 224901020486,24.14318315845238 4
</gml:coordinates>
</gml:LinearRing>
</gml:outerBoundaryIs>
</gml:Polygon>
</gml:polygonMember>
</gml:MultiPolygon>
</WFS:Shape>
<WFS:CITY>臺中市</WFS:CITY>
<WFS:SECT>0008</WFS:SECT>
<WFS:LANDNO>00010000</WFS:LANDNO>
<WFS:OFFICE>BA</WFS:OFFICE>
<WFS:TOWN>中區</WFS:TOWN>
<WFS:AREA>119.0</WFS:AREA>
<WFS:LANDUSE/><WFS:LANDDETATIS/>
<WFS:VALUESSESSED>80882</WFS:VALUESSESSED>
<WFS:VALUEANNOUNCE>22659</WFS:VALUEANNOUNCE>
</WFS:CADASTRE>
</gml:featureMember>
</FeatureCollection>

二、指定坐標查詢地籍圖

(一) URL

https://api.nlsc.gov.tw/dmaps/CadasMapPointQuery

URI	HTTP Method
/CadasMapPointQuery/{X 坐標}/{Y 坐標}/	GET
/CadasMapPointQuery/{X 坐標}/{Y 坐標}/{坐標類別代碼}	GET
/CadasMapPointQuery/{X 坐標}/{Y 坐標}/{坐標類別代碼}/{檔案格式}	

(二) 傳入參數說明

編碼：UTF-8

輸入參數	預設值	說明
{X 坐標}		查詢點的 X 坐標
{Y 坐標}		查詢點的 Y 坐標
{坐標類別代碼}	EPSG4326	EPSG4326 (WGS84) EPSG3825 (TWD97/TM2 Zone119(澎湖)) EPSG3826 (TWD97/TM2 Zone121(臺灣))
{檔案格式}	GML	gml, kml, shp

(三) 回傳格式：GML(預設)、KML、SHP

編碼：UTF-8

參照 GML(Geography Markup Language)、KML（Keyhole

Markup Language）、SHP（ESRI Shapefile）格式。

。

(四) 範例

Request
https://api.nlsc.gov.tw/dmaps/CadasMapPointQuery/120.200933/23.043319
Response


```
<?xml version="1.0" encoding="UTF-8" standalone="no"?>
<FeatureCollection xmlns:WFS="https://www.opengis.net/wfs" xmlns:gml=
"https://www.opengis.net/gml" xmlns:wfs="https://www.opengis.net/wfs">
  <gml:boundedBy>
    <gml:Box srsName="EPSG:4326">
      <gml:coordinates>120.20088053189446,23.043303642221773 120.2
009617211113,23.043331077083028</gml:coordinates>
    </gml:Box>
  </gml:boundedBy>
  <gml:featureMember>
    <WFS:CADASTRE fid="1">
      <WFS:Shape>
        <gml:MultiPolygon>
          <gml:polygonMember>
            <gml:Polygon srsName="EPSG:4326">
              <gml:outerBoundaryIs>
                <gml:LinearRing>
                  <gml:coordinates>120.20088277990494,23.043331077
083028 120.20088053189446,23.043321504663318 120.2009617211113,23.
043303642221773 120.20095394542258…
</gml:coordinates>
                </gml:LinearRing>
              </gml:outerBoundaryIs>
            </gml:Polygon>
          </gml:polygonMember>
        </gml:MultiPolygon>
      </WFS:Shape>
      <WFS:CITY>臺南市</WFS:CITY>
      <WFS:SECT>0259</WFS:SECT>
      <WFS:LANDNO>09400000</WFS:LANDNO>
      <WFS:OFFICE>DB</WFS:OFFICE>
      <WFS:TOWN>安南區</WFS:TOWN>
      <WFS:AREA>8.55</WFS:AREA>
      <WFS:LANDUSE/>
      <WFS:LANDDETATIS/>
```

```
        <WFS:VALUESSESSED>34100</WFS:VALUESSESSED>
        <WFS:VALUEANNOUNCE>6500</WFS:VALUEANNOUNCE>
      </WFS:CADASTRE>
    </gml:featureMember>
</FeatureCollection>
```


第三節 地籍 API 服務

一、指定地號查詢位置

(一) URL

https://api.nlsc.gov.tw/dmaps/CadasMapPosition/

URI	HTTP Method
/CadasMapPosition/{縣市代碼}/{地段代碼}/{地號}	GET
/CadasMapPosition/{縣市代碼}/{地段代碼}/{地號}/{結果坐標系}	GET

(二) 傳入參數說明

編碼：UTF-8

輸入參數	預設值	說明
{縣市代碼}		必填，以英文 1 碼表示，由 A~Z 組成
{地段代碼}		必填，以數字 4 碼組成
{完整地號}		必填，以數字 8 碼組成
{坐標類別代碼}	EPSG4326	EPSG4326 (WGS84) EPSG3825 (TWD97/TM2 Zone119(澎湖)) EPSG3826 (TWD97/TM2 Zone121(臺灣))

(三) 回傳格式：application/xml

編碼：UTF-8

Parent Node	Node	Value
<cadsPositionItem>	<repX>	代表點橫坐標（X）
	<repY>	代表點縱坐標（X）
	<ldX>	左下橫坐標（X）
	<ldY>	左下點縱坐標（X）
	<rtX>	右上橫坐標（X）
	<rtY>	右上點縱坐標（X）

(四) 範例

Request
https://api.nlsc.gov.tw/dmaps/CadasMapPosition/B/0012/00010000
Response
<cadsPositionItem> <repX>120.683552</repX> <repY>24.142313</repY> <ldX>120.683471</ldX> <ldY>24.142235</ldY> <rtX>120.683633</rtX> <rtY>24.142389</rtY> </cadsPositionItem>

二、指定地號查詢著色

(一) URL

https://api.nlsc.gov.tw/dmaps/CadasMapImage

URI	HTTP Method
/CadasMapImage/{縣市代碼}/{地段代碼}/{地號(8碼)}/	GET

(二) 傳入參數說明

編碼：UTF-8

輸入參數	預設值	說明
{縣市代碼}		必填，以英文 1 碼表示，由 A~Z 組成，例如：A=臺北市
{地段代碼}		必填，以數字 4 碼組成
{完整地號}		必填，以數字 8 碼組成

(三) 回傳格式：application/JSON

編碼：UTF-8

代碼	說明
lx	左下經度坐標（X）
ly	左下緯度坐標（Y）
rx	右上經度坐標（X）
ry	右上緯度坐標（Y）
image	地號著色影像檔，圖片(Base64)

(四) 範例

Request
https://api.nlsc.gov.tw/dmaps/CadasMapImage/B/0012/00010000
Response

{
"lx":120.62604418753313,
"ly":24.14645057108406,
"rx":120.62620681522012,
"ry":24.14660443074493,
"image":"iVBORw0KGgoAAAANSUhEUgAAAQAAAAEACAYAAA
BccqhmAAAEHUlEQVR42u3aUYoCMRRFwew8S2/9UBBBs
FWQ5NSBu4GBeo7BMaTNm2Mc/…/AAAAAElFTkSuQmC
C"
}

三、單點坐標查詢地段號

(一) URL

https://landmaps.nlsc.gov.tw/S_Maps_WebService/qryLand/

https://landmaps.nlsc.gov.tw/S_Maps_WebService/qryLand?

https://api.nlsc.gov.tw/S_Maps_WebService/qryLand/

https://api.nlsc.gov.tw/S_Maps_WebService/qryLand?

URI	HTTP Method
/GetLandNO/ {經度}/{緯度}	GET
xml=<SQUIDReq><ServiceReq><Body><QueryRequest><QueryType>GetLandNO</QueryType><Longitude>{經度}</Longitude><Latitude>{緯度}</Latitude></QueryRequest></Body></ServiceReq></SQUIDReq>	POST

(二) 傳入參數說明

編碼：UTF-8

輸入參數	預設值	說明
{經度}		必填，WGS84 經度
{緯度}		必填，WGS84 緯度

(三) 回傳格式：application/xml

編碼：BIG5

Parent Node	Node	Value
<RESPONSE>	<CITY>	縣市代碼
	<SEC>	地段代碼
	<NO>	完整地號
	<STATUS>	查詢狀態

(四) 範例

Request
https://landmaps.nlsc.gov.tw/S_Maps_WebService/qryLand/GetLandNO/120.634413/24.133282
Response
<?xml version="1.0" encoding="BIG5" standalone="no"?> <LISERVICERSGMSG> <STATUS>0</STATUS> <MESSAGE/> <RETURNROWS>1</RETURNROWS> <RESPONSE> <QUERYTYPE>GETLANDNO</QUERYTYPE> <CITY>B</CITY> <SEC>2013</SEC> <NO>03420000</NO> <STATUS>OK</STATUS> </RESPONSE> </LISERVICERSGMSG>

四、地段號查詢坐標

(一) URL

https://landmaps.nlsc.gov.tw/S_Maps_WebService/qryLand/

https://landmaps.nlsc.gov.tw/S_Maps_WebService/qryLand?

https://api.nlsc.gov.tw/S_Maps_WebService/qryLand/

https://api.nlsc.gov.tw/S_Maps_WebService/qryLand?

URI	HTTP Method
/GetLandPositionLongitudeLatitude/{縣市代碼}/{地段代碼}/{地號}	GET
xml=<SQUIDReq><ServiceReq><Body><QueryRequest><QueryType>GetLandPositionLongitudeLatitude</QueryType><City>{縣市代碼}</City><Sec>{地段代碼}</Sec><No>{地	POST

號}</No></QueryRequest></Body></ServiceReq></SQUIDReq>	

(二) 傳入參數說明

編碼：UTF-8

輸入參數	預設值	說明
{縣市代碼}		必填，以英文 1 碼表示，由 A~Z 組成，例如：A=臺北市
{地段代碼}		必填，以數字 4 碼組成
{完整地號}		必填，以數字 8 碼組成

(三) 回傳格式：application/xml

編碼：BIG5

Parent Node	Node	Value
<RESPONSE>	<LONGITUDE>	經度
	<LATITUDE>	緯度
	<STATUS>	查詢狀態

(四) 範例

Request
https://landmaps.nlsc.gov.tw/S_Maps_WebService/qryLand/GetLandPositionLongitudeLatitude/B/1622/05090000
Response
<?xml version="1.0" encoding="BIG5" standalone="no"?> <LIServiceRsgMsg> <STATUS>0</STATUS> <MESSAGE/> <RETURNROWS>1</RETURNROWS> <RESPONSE> <QUERYTYPE>GETLANDPOSITIONLONGITUDELATITUDE</QUERYTYPE> <LONGITUDE>120.631804</LONGITUDE> <LATITUDE>24.184695</LATITUDE> <STATUS>OK</STATUS>

```
    </RESPONSE>
</LIServiceRsgMsg
```

五、坐標查地段號

(一) URL

https://api.nlsc.gov.tw/S_Maps/qryTileMapIndex?

https://landmaps.nlsc.gov.tw/S_Maps/qryTileMapIndex?

URI	HTTP Method
type=2&flag=1&city={縣市代碼}&x={經度}&y={緯度}	GET

(二) 傳入參數說明

編碼：UTF-8

輸入參數	預設值	說明
{type}		必填，功能參數 type=2
{flag }		必填，功能參數 flag=1
{縣市代碼}		必填,以英文 1 碼表示,由 A~Z 組成，例如：A=臺北市
{經度}		必填，WGS84 經度
{緯度}		必填，WGS84 緯度

(三) 回傳格式：application/JSON

編碼：UTF-8

代碼	說明
sectStr	地段中文（Base64）
sect	地段代碼（4 碼）
officeStr	地所中文（Base64）
office	地所代碼（2 碼）

landno	完整地號（8 碼）
cx	中心點經度坐標（X）
cy	中心點緯度坐標（Y）
lx	左下經度坐標（X）
ly	左下緯度坐標（Y）
rx	右上經度坐標（X）
ry	右上緯度坐標（Y）
extend	段延伸碼

(四) 範例

Request
https://api.nlsc.gov.tw/S_Maps/qryTileMapIndex?type=2&flag=1&city=B&x=120.634413&y=24.153282
Response


```
[
  {
    "sectStr": "6buO5piO5q61",
    "sect": "2013",
    "officeStr": "5Lit6IiI",
    "office": "BC",
    "landno": "03420000",
    "cx": 120.633943,
    "cy": 24.153468,
    "lx": 120.633053,
    "ly": 24.152829,
    "rx": 120.634835,
    "ry": 24.153634,
    "extend": "0"
  }
]
```


六、地段號宗地定位

(一) URL

https://api.nlsc.gov.tw/S_Maps/qryTileMapIndex?

https://landmaps.nlsc.gov.tw/S_Maps/qryTileMapIndex?

URI	HTTP

	Method
type=2&flag=2&office={地所代碼}&sect={地段代碼}&landno={完整地號}	GET

(二) 傳入參數說明

編碼：UTF-8

輸入參數	預設值	說明
{type}		必填，功能參數 type=2
{flag }		必填，功能參數 flag=2
{地所代碼}		必填,以英文 2 碼表示,由 A~Z 組成，第 1 碼為縣市代碼
{地段代碼}		必填，以數字 4 碼組成
{完整地號}		必填，以數字 8 碼組成

(三) 回傳格式：application/JSON

編碼：UTF-8

代碼	說明
sectStr	地段中文（Base64）
sect	地段代碼（4 碼）
officeStr	地所中文（Base64）
office	地所代碼（2 碼）
landno	完整地號（8 碼）
cx	中心點經度坐標（X）
cy	中心點緯度坐標（Y）
lx	左下經度坐標（X）
ly	左下緯度坐標（Y）
rx	右上經度坐標（X）
ry	右上緯度坐標（Y）

(四) 範例

Request

https://api.nlsc.gov.tw/S_Maps/qryTileMapIndex?type=2&flag=2&office=BC&sect=2013&landno=03420000
Response

[
{
"sectStr": "6buO5piO5q61",
"sect": "2013",
"officeStr": "5Lit6IiI",
"office": "BC",
"landno": "03420000",
"cx": 120.633943,
"cy": 24.153468,
"lx": 120.633053,
"ly": 24.152829,
"rx": 120.634835,
"ry": 24.153634
}
]

七、指定地號查詢土地標示資料

(一) URL

https://api.nlsc.gov.tw/dmaps/CadasAttrQuery/

URI	HTTP Method
/CadasAttrQuery/{縣市代碼}/{地段代碼}/{地號}	GET

(二) 傳入參數說明

編碼：UTF-8

輸入參數	預設值	說明
{縣市代碼}		必填，以英文 1 碼表示，由 A~Z 組成，例如：A=臺北市
{地段代碼}		必填，以數字 4 碼組成
{完整地號}		必填，以數字組成，可輸入完整地號 8 碼；或者輸入簡易地

		號

(三) 回傳格式：application/json

編碼：UTF-8

代碼	說明
AA05	登記日期
AA10	面積
AA11	使用分區
AA12	使用地類別
AA16	公告現值
AA17	公告地價

(四) 範例

Request
https://api.nlsc.gov.tw/dmaps/CadasAttrQuery/B/8056/892
Response

[
{
"AA05": "0540415",
"AA10": 5625.32,
"AA11": "AC",
"AA12": "EP",
"AA16": 27500,
"AA17": 3600
}
]

八、地段代碼回傳測繪段籍屬性

(一) URL

https://api.nlsc.gov.tw/other/

URI	HTTP

	Method
/GetLandSecInfoNlsc/{縣市代碼}/{地段代碼}/{段延伸碼}	GET

(二) 傳入參數說明

編碼：UTF-8

輸入參數	預設值	說明
{縣市代碼}		必填，以英文 1 碼表示，由 A~Z 組成，例如：A=臺北市
{地段代碼}		必填，以數字 4 碼組成
{段延伸碼}		段延伸碼 1 碼

(三) 回傳格式：application/xml

編碼：UTF-8

Parent Node	Node	Value
	CITY	縣市名稱
	LDCODE	地政事務所名稱
	SCNO	段代碼
	SCNOEXT	段延伸碼
	TOWN	鄉鎮市區代碼
	SVWAY	測量方法
	SVTYPE	測量類別
	MYEAR	成圖年度
	MMONTH	成圖月份
	COOR	坐標系統
	WORNST	破損情形
	ERRST	誤謬情形
	SCALE	比例尺

	DDATE	數化日期
	rYear	預計重測年度

(四) 範例

Request
https://api.nlsc.gov.tw/dmaps/GetLandSecInfoNlsc/B/0001/0
Response
<?xml version="1.0" encoding="UTF-8" standalone="no"?> <SysdatSecBean> <city>臺中市</city> <ldcode>中山</ldcode> <scNo>0001</scNo> <scNoExt>0</scNoExt> <town>01</town> <scnMext/> <svway>2</svway> <svType>4</svType> <mYear>50</mYear> <mMonth>12</mMonth> <coor>3</coor> <wornst>0</wornst> <errst>0</errst> <slprt>0.0</slprt> <urbnrt>0.0</urbnrt> <rplrt>0.0</rplrt> <scale>600</scale> <dDate>8812</dDate> <rYear>0</rYear> </SysdatSecBean>

九、指定地號查詢位置

(一) URL

https://api.nlsc.gov.tw/idc/AddressQueryLand/

URI	HTTP Method
/AddressQueryLand/{搜尋字串}	GET
/ AddressQueryLand /{搜尋字串}/{回傳數量}	GET

(二) 傳入參數說明

編碼：UTF-8

輸入參數	預設值	說明
{搜尋字串}		欲查詢之戶政門牌號碼
{回傳數量}	1	選取檢索結果最接近的筆數 (最大 25 筆)

(三) 回傳格式：application/xml

編碼：UTF-8

Parent Node	Node	Value
<addressItems> <addressItem>	<content>	完整戶政門牌號碼
	<location>	圖資位置（經緯度）
	<office>	地所代碼（2 碼）
	<sect>	地段代碼（4 碼）
	<landno>	完整地號（8 碼）

(四) 範例

Request
https://api.nlsc.gov.tw/idc/AddressQueryLand/台中市南屯區黎明路二段 497 號
Response
<addressItems> <addressItem> <content>臺中市南屯區黎明里００１鄰黎明路二段４９７號</content> <location>120.634421,24.153412</location> <office>BC</office> <sect>2013</sect> <landno>03420000</landno> </addressItem>

</addressItems>

十、指定範圍查詢地號清單

(一) URL

https://api.nlsc.gov.tw/dmaps/CadasLandNoQuery/

URI	HTTP Method
/CadasLandNoQuery/{多邊形坐標}/	GET
/CadasLandNoQuery/{多邊形坐標}/{坐標類別代碼}	GET
/CadasLandNoQuery/{多邊形坐標}/{坐標類別代碼}/{判定方式}	GET

(二) 傳入參數說明

編碼：UTF-8

輸入參數	預設值	說明
{多邊形坐標}		必填，由三組以上的橫縱坐標（X 坐標,Y 坐標）組成，各組坐標間以透點隔開，如：x1,y1,x2,y2, ...xn,yn
{坐標類別代碼}	EPSG4326	EPSG4326 (WGS84) EPSG3825 (TWD97/TM2 Zone119) EPSG3826 (TWD97/TM2 Zone121)
{判定方式}		預設未填為相交，填 WithIn 為內含

(三) 回傳格式：application/json

編碼：UTF-8

代碼	說明
city	縣市代碼（1 碼）

sect	地段代碼（4 碼）
landList	地號清單，統一以完整地號顯示（8 碼），各地號間以透點隔開

(四) 範例

Request
https://api.nlsc.gov.tw/dmaps/CadasLandNoQuery/120.681375,24.178507,120.682373,24.176020,120.686611,24.177293/4326/WithIn
Response

[
{
"city": "B",
"sect": "1118",
"landList": [
"09770001",
"09770002",
"09770003",
"09770004",
"09770005",
"09770006"
]
}
]

十一、指定地號查詢建號列表與土地權利人類別

(一) URL

https://api.nlsc.gov.tw/dmaps/CadasLandInfo/

URI	HTTP Method
/CadasLandInfo/{縣市代碼}/{地段代碼}/{地號}	GET

(二) 傳入參數說明

編碼：UTF-8

輸入參數	預設值	說明
{縣市代碼}		必填，以英文 1 碼表示，由 A~Z 組成，例如：A=臺北市
{地段代碼}		必填，以數字 4 碼組成
{地號}		必填，支援完整地號（8 碼）及簡易地號

(三) 回傳格式：application/json

編碼：UTF-8

代碼	說明
buildList	建號清單，統一以完整建號顯示（8 碼），各建號間以透點隔開
ownerType	土地所有權人類別及比例，多組以透點隔開，比例四捨五入取至小數點第二位

(四) 範例

Request
https://api.nlsc.gov.tw/dmaps/CadasLandInfo/B/1121/8
Response


```
{
        "buildList": [
          "02906000",
          "02907000",
          "02908000",
          "02909000",
          "02910000",
          "02911000",
          "02912000"
        ],
        "ownerType": {
          "銀行法人": "0.14%",
          "外國人": "0.36%",
```

```
            "本國人": "99.25%",
            "本國私法人": "0.25%"
        }
}
```


第四節 國土利用 API 服務

一、指定國土利用現況調查成果圖比較

(一) URL

https://api.nlsc.gov.tw/other/LandUseCompare/

URI	HTTP Method
/LandUseCompare/{年度 1}/{年度 2}/{鄉鎮市區代碼}	GET
/LandUseCompare/{年度 1}/{年度 2}/{X1 坐標,Y1 坐標}/{X2 坐標, Y2 坐標}/	GET

(二) 傳入參數說明

編碼：UTF-8

輸入參數	預設值	說明
{年度 1}		必填，比較年度(新)
{年度 2}		必填，比較年度(舊)
{鄉鎮市區代碼}		鄉鎮市區 3 碼
{X1 坐標,Y1 坐標}		範圍矩框的左下坐標（經緯度 WGS84）
{X2 坐標, Y2 坐標}		範圍矩框的右上坐標（經緯度 WGS84）

(三) 回傳格式：application/xml

編碼：UTF-8

Parent Node	Node	Value
<Change>	<County>	縣市代碼
	<Town>	鄉鎮市區代碼
	<Code2Before>	年度 2 分類代碼
	<Code2After>	年度 1 分類代碼
	<Area>	變遷面積 (單位 0.09 m2)
<LandUseCompare>	<ImageURL>	變遷圖 URL
	<ImageRect>	變遷圖極值

(四) 範例

Request
https://api.nlsc.gov.tw/other/LandUseCompare/104/098/120.158057,23.760275/120.165543,23.769345/
Response
<LandUseCompare> <Change> <County>P</County> <Town>P13</Town> <Code2Before>0202</Code2Before> <Code2After>0303</Code2After> <Area>156</Area> </Change> <Change> <County>P</County> <Town>P13</Town> <Code2Before>0202</Code2Before> <Code2After>0601</Code2After> <Area>1219</Area> </Change> … <ImageURL> http://api.nlsc.gov.tw/LuiCompareImg/20220418102800116137.png </ImageURL> <ImageRect>120.15505,23.76027,120.16854,23.76934</ImageRect> </LandUseCompare>

二、歷年(或指定年分)國土利用現況調查成果圖屬性

(一) URL

https://api.nlsc.gov.tw/other/LandUsePointYears/

URI	HTTP Method
/LandUsePointYears/{指定年分}/{X 坐標}/{Y 坐標}/	GET
/LandUsePointYears/{指定年分}/{X 坐標}/{Y 坐標}/{坐標類別代碼}	GET

(二) 傳入參數說明

編碼：UTF-8

輸入參數	預設值	說明
{指定年分}		必填，民國年（輸入 0 為歷年）
{X 坐標}		必填，查詢點的 X 坐標
{Y 坐標}		必填，查詢點的 Y 坐標
{坐標類別代碼}	EPSG4326	EPSG4326 (WGS84) EPSG3825 (TWD97/TM2 Zone119(澎湖)) EPSG3826 (TWD97/TM2 Zone121(臺灣))

(三) 回傳格式：application/xml

編碼：UTF-8

Parent Node	Node	Value
<ITEM>	<YEAR>	圖磚年度
	<LYEAR>	調查年度
	<LMONTH>	調查月份
	<Lcode_C1>	一級分類代碼
	<Lname_C1>	一級分類中文說明
	<Lcode_C2>	二級分類代碼
	<Lname_C2>	二級分類中文說明
	<Lcode_C3>	三級分類代碼
	<LCODE>	最高分級代碼
	<NAME>	最高分級中文說明

(四) 範例

Request

https://api.nlsc.gov.tw/other/LandUsePointYears/0/120.634413/24.153282/4326

Response


```
<ITEM>
        <YEAR>106</YEAR>
        <LYEAR>2017</LYEAR>
        <LMONTH>11</LMONTH>
        <Lcode_C1>06</Lcode_C1>
        <Lname_C1>公共利用土地</Lname_C1>
        <Lcode_C2>0601</Lcode_C2>
        <Lname_C2>政府機關</Lname_C2>
        <Lcode_C3>060100</Lcode_C3>
        <LCODE>060100</LCODE>
        <NAME>政府機關</NAME>
</ITEM>
<ITEM>
        <YEAR>108</YEAR>
        <LYEAR>2019</LYEAR>
        <LMONTH>11</LMONTH>
        <Lcode_C1>06</Lcode_C1>
        <Lname_C1>公共利用土地</Lname_C1>
        <Lcode_C2>0601</Lcode_C2>
        <Lname_C2>政府機關</Lname_C2>
        <Lcode_C3>060100</Lcode_C3>
        <LCODE>060100</LCODE>
        <NAME>政府機關</NAME>
</ITEM>
```

第五節 路徑規劃 API 服務

一、路徑規劃(距離最短)服務

(一) URL

https://api.nlsc.gov.tw/other/RoutesQueryByDist/

URI	HTTP Method
/RoutesQueryByDist/{起點(WGS84)}/{終點(WGS84)}	GET
/RoutesQueryByDist/{起點(WGS84)}/{終點(WGS84)}/{車種}	GET
/RoutesQueryByDist/{起點(WGS84)}/{終點(WGS84)}/{車種}/{檔案格式}	GET
/RoutesQueryByDist/{起點(WGS84)}/{終點(WGS84)}/{車種}/{檔案格式}/{障礙點}	GET

(二) 傳入參數說明

編碼：UTF-8

輸入參數	預設值	說明
{起點(WGS84)}		經緯度{X 坐標,Y 坐標}
{終點(WGS84)}		經緯度{X 坐標,Y 坐標}
{車種}	car	car(汽車)、foot(步行)、avoid_highways(汽車避開高速公路)，預設為汽車
{檔案格式}	kmz	kmz、json、kml
{障礙點}		Barrier，WGS84 可輸入多筆

(三) 回傳格式：application/ kmz

編碼：UTF-8

Parent Node	Node	Value
<Document> <ExtendedData>	<Data name="duration">	總時間(秒)
	<Data name="distance ">	總距離(公尺)
<Placemark> <ExtendedData>	<Data name="turnDirection">	轉向
	<Data name="road">	路名
	<Data name="duration">	該步驟的時間(秒)
	<Data name="distance">	該步驟的距離(公尺)

(四) 範例

Request
https://api.nlsc.gov.tw/other/RoutesQueryByDist/120.63448,24.1534566/120.66591498,24.15608765/car/json?barrier=120.649777,24.153601,120.640695,24.153661
Response


```
<kml  xmlns="https://www.opengis.net/kml/2.2">
  <Document>
    <ExtendedData>
      <Data  name="duration">
        <value>537</value>
      </Data>
      <Data  name="distance">
        <value>3889</value>
      </Data>
    </ExtendedData>
    <Placemark>
      <name>步驟 0</name>
      <visibility>1</visibility>
      <LineString>
        <coordinates>120.634471680229,24.1536927109896,0.0  120.634662559997,24.153698371271,0.0  120.634822399984,24.1537775156709,0.0</coordinates>
      </LineString>
      <ExtendedData>
```

```
            <Data  name="turnDirection">
               <value>前進</value>
            </Data>
            <Data  name="road">
               <value>大業路</value>
            </Data>
            <Data  name="duration">
               <value>5</value>
            </Data>
            <Data  name="distance">
               <value>38</value>
            </Data>
         </ExtendedData>
      </Placemark>
      <Placemark>
         <name>步驟 1</name>
         <visibility>1</visibility>
         <LineString>
            <coordinates>120.634822399984,24.1537775156709,0.0  120.6349552
39999,24.1537793705052,0.0  120.635307320003,24.1537584488971,0.0  120.6
35497890007,24.1537326175406,0.0  120.635835300015,24.1536674749278,0.0
 120.636191729994,24.1535949622851,0.0  120.636375379999,24.1535737004
628,0.0  120.636680659992,24.1535914630106,0.0  120.636822719992,24.1536
096528151,0.0</coordinates>
         </LineString>
         <ExtendedData>
            <Data  name="turnDirection">
               <value>右轉</value>
            </Data>
            <Data  name="road">
               <value>大業路</value>
            </Data>
            <Data  name="duration">
               <value>29</value>
            </Data>
            <Data  name="distance">
               <value>206</value>
            </Data>
         </ExtendedData>
      </Placemark>
…
```


二、路徑規劃(時間最短)服務

(一) URL

https://api.nlsc.gov.tw/other/RoutesQueryByTime/

URI	HTTP Method
/RoutesQueryByTime/{起點(WGS84)}/{終點(WGS84)}	GET
/RoutesQueryByTime/{起點(WGS84)}/{終點(WGS84)}/{車種}	GET
/RoutesQueryByTime/{起點(WGS84)}/{終點(WGS84)}/{車種}/{檔案格式}	GET
/ RoutesQueryByTime/{起點(WGS84)}/{終點(WGS84)}/{車種}/{檔案格式}/{障礙點}	GET

(二) 傳入參數說明

編碼：UTF-8

輸入參數	預設值	說明
{起點(WGS84)}		必填，經緯度{X 坐標,Y 坐標}
{終點(WGS84)}		必填，經緯度{X 坐標,Y 坐標}
{車種}	car	car(汽車)、foot(步行)、avoid_highways(汽車避開高速公路)，預設為汽車
{檔案格式}	kmz	kmz、json、kml
{障礙點}		Barrier，WGS84 可輸入多筆

(三) 回傳格式：application/ kmz

編碼：UTF-8

Parent Node	Node	Value
<Document> <ExtendedData>	<Data name="duration">	總時間(秒)
	<Data name="distance ">	總距離(公尺)
<Placemark> <ExtendedData>	<Data name="turnDirection">	轉向
	<Data name="road">	路名
	<Data name="duration">	該步驟的時間

		(秒)
	<Data name="distance">	該步驟的距離(公尺)

(四) 範例

Request
https://api.nlsc.gov.tw/other/RoutesQueryByTime/120.63448,24.1534566/120.66591498,24.15608765/car/json?barrier=120.649777,24.153601,120.640695,24.153661

Response


```
<kml xmlns="https://www.opengis.net/kml/2.2">
  <Document>
    <ExtendedData>
      <Data name="duration">
        <value>537</value>
      </Data>
      <Data name="distance">
        <value>3889</value>
      </Data>
    </ExtendedData>
    <Placemark>
      <name>步驟 0</name>
      <visibility>1</visibility>
      <LineString>
        <coordinates>120.634471680229,24.1536927109896,0.0 120.634662559997,24.153698371271,0.0 120.634822399984,24.1537775156709,0.0</coordinates>
      </LineString>
      <ExtendedData>
        <Data name="turnDirection">
          <value>前進</value>
        </Data>
        <Data name="road">
          <value>大業路</value>
        </Data>
        <Data name="duration">
          <value>5</value>
        </Data>
        <Data name="distance">
          <value>38</value>
        </Data>
      </ExtendedData>
    </Placemark>
```

```
      <Placemark>
        <name>步驟 1</name>
        <visibility>1</visibility>
        <LineString>
          <coordinates>120.634822399984,24.1537775156709,0.0  120.63495523
9999,24.1537793705052,0.0  120.635307320003,24.1537584488971,0.0  120.635
497890007,24.1537326175406,0.0  120.635835300015,24.1536674749278,0.0  12
0.636191729994,24.1535949622851,0.0  120.636375379999,24.1535737004628,
0.0  120.636680659992,24.1535914630106,0.0  120.636822719992,24.153609652
8151,0.0</coordinates>
        </LineString>
        <ExtendedData>
          <Data  name="turnDirection">
            <value>右轉</value>
          </Data>
          <Data  name="road">
            <value>大業路</value>
          </Data>
          <Data  name="duration">
            <value>29</value>
          </Data>
          <Data  name="distance">
            <value>206</value>
          </Data>
        </ExtendedData>
      </Placemark>
…
```


三、路徑規劃之節點查詢

(一) URL

https://api.nlsc.gov.tw/other/RoutesNodes/

URI	HTTP Method
/RoutesNodes/{查詢點}	GET
/RoutesNodes/{查詢點}/{坐標代碼}	GET
/RoutesNodes/{查詢點}/{坐標代碼}/{檢索範圍}	GET

(二) 傳入參數說明

編碼：UTF-8

輸入參數	預設值	說明
{查詢點}		必填，{X 坐標,Y 坐標}
{坐標代碼}	EPSG:4326	EPSG:4326 (WGS84) EPSG:3826 (TWD97)
{檢索範圍}	500	查詢方框半徑，最大允許可指定值為 12500 (公尺)

(三) 回傳格式：text/plain

編碼：UTF-8，回傳內容由近到遠排序。假設回結果有的 n 個節點 v1,v2,⋯,vn 則文字內容為 v1.x,v1.y,v2.x,v2.y,⋯,vn.x,vn.y。

(四) 範例

Request
https://api.nlsc.gov.tw/other/RoutesNodes/120.630656,24.150840/EPSG:4326/500
Response
120.6308088,24.15081098,120.63081011,24.15091437,120.63058729,24.15108972,120.63063074,24.15135997,120.63080095,24.1501883,120.63017707,24.15146231,120.631169,24.15146743,120.63113547,24.15161921,120.62989026,24.1515623,120.63057546,24.15196447,120.63037955,24.15196056,120.63181001,24.150985509999998, …

第六節 開放 API 服務

一、單點坐標回傳行政區（地政）

(一) URL

https://api.nlsc.gov.tw/other/TownVillagePointQuery

URI	HTTP Method
../{X 坐標}/{Y 坐標}	GET
../{X 坐標}/{Y 坐標}/{坐標類別代碼}	GET

(二) 傳入參數說明

編碼：UTF-8

輸入參數	預設值	說明
{X 坐標}		必填，查詢點的 X 坐標
{Y 坐標}		必填，查詢點的 Y 坐標
{坐標類別代碼}	EPSG4326	EPSG4326 (WGS84) EPSG3825 (TWD97/TM2 Zone119(澎湖)) EPSG3826 (TWD97/TM2 Zone121(臺灣))

(三) 回傳格式：application/xml

編碼：UTF-8

Parent Node	Node	Value
<townVillageItem>	<ctyCode>	縣市代碼（地政）
	<ctyName>	縣市名稱
	<townCode>	鄉鎮市區代碼（地政）
	<townName>	鄉鎮市區名稱
	<officeCode>	地政事務所代碼
	<officeName>	地政事務所名稱
	<sectCode>	地段代碼
	<sectName>	地段名稱
	<villageCode>	村里代碼
	<villageName>	村里名稱

(四) 範例

Request
https://api.nlsc.gov.tw/other/TownVillagePointQuery/120.634413/

24.153282/4326
Response
<?xml version="1.0" encoding="UTF-8" standalone="yes"?> <townVillageItem> <ctyCode>B</ctyCode> <ctyName>臺中市</ctyName> <townCode>B07</townCode> <townName>南屯區</townName> <officeCode>BC</officeCode> <officeName>中興</officeName> <sectCode>2013</sectCode> <sectName>黎明段</sectName> <villageCode>66000070013</villageCode> <villageName>黎明里</villageName> </townVillageItem>

二、單點坐標回傳行政區（戶政）

(一) URL

https://api.nlsc.gov.tw/other/TownVillagePointQuery1

URI	HTTP Method
../{X 坐標}/{Y 坐標}	GET
../{X 坐標}/{Y 坐標}/{坐標類別代碼}	GET

(二) 傳入參數說明

編碼：UTF-8

輸入參數	預設值	說明
{X 坐標}		必填，查詢點的 X 坐標
{Y 坐標}		必填，查詢點的 Y 坐標
{坐標類別代碼}	EPSG4326	EPSG4326 (WGS84) EPSG3825 (TWD97/TM2 Zone119(澎湖))

		EPSG3826 (TWD97/TM2 Zone121(臺灣))

(三) 回傳格式：application/xml

編碼：UTF-8

Parent Node	Node	Value
<townVillageItem>	<ctyCode>	縣市代碼（戶政）
	<ctyName>	縣市名稱
	<townCode>	鄉鎮市區代碼（戶政）
	<townName>	鄉鎮市區名稱
	<villageCode>	村里代碼
	<villageName>	村里名稱

(四) 範例

Request
https://api.nlsc.gov.tw/other/TownVillagePointQuery1/120.635324/24.030304/4326
Response
<townVillageItem> <ctyCode>10007</ctyCode> <ctyName>彰化縣</ctyName> <townCode>10007090</townCode> <townName>芬園鄉</townName> <villageCode>10007090005</villageCode> <villageName>茄苳村</villageName> </townVillageItem>

三、代碼服務－縣市清單

(一) URL

https://api.nlsc.gov.tw/other/ListCounty/

(二) 傳入參數說明

無。

(三) 回傳格式：application/xml

編碼：UTF-8

Parent Node	Node	Value
<countyItem>	<countycode>	縣市代碼
	<countyname>	縣市名稱

(四) 範例

Request
https://api.nlsc.gov.tw/other/ListCounty/
Response
<?xml version="1.0" encoding="UTF-8" standalone="yes"?> <countyItems> <countyItem> <countycode>A</countycode> <countyname>臺北市</countyname> </countyItem> <countyItem> <countycode>B</countycode> <countyname>臺中市</countyname> </countyItem> …

四、代碼服務－鄉鎮市區清單（地政）

(一) URL

https://api.nlsc.gov.tw/other/ListTown

URI	HTTP Method
../{縣市代碼}	GET

(二) 傳入參數說明

編碼：UTF-8

輸入參數	預設值	說明
{縣市代碼}		必填，以英文 1 碼表示，由 A~Z 組成，例如：A=臺北市

(三) 回傳格式：application/xml

編碼：UTF-8

Parent Node	Node	Value
<townItem>	<towncode>	鄉鎮市區代碼
	<townname>	鄉鎮市區名稱

(四) 範例

Request
https://api.nlsc.gov.tw/other/ListTown/I/
Response
<townItems> <townItem> <towncode>I01</towncode> <townname>嘉義市</townname> </townItem> </townItems>

五、代碼服務－鄉鎮市區清單（戶政）

(一) URL

https://api.nlsc.gov.tw/other/ListTown1

URI	HTTP Method
../{縣市代碼}	GET

(二) 傳入參數說明

編碼：UTF-8

輸入參數	預設值	說明
{縣市代碼}		必填，以英文 1 碼表示，由 A~Z 組成，例如：A=臺北市

(三) 回傳格式：application/xml

編碼：UTF-8

Parent Node	Node	Value
<townItem>	<towncode>	鄉鎮市區代碼（戶政）
	<towncode01>	鄉鎮市區代碼（地政）
	<townname>	鄉鎮市區名稱

(四) 範例

Request
https://api.nlsc.gov.tw/other/ListTown1/I/
Response

```
<townItems>
        <townItem>
            <towncode>10020010</towncode>
            <towncode01>I01</towncode01>
            <townname>東區</townname>
        </townItem>
        <townItem>
            <towncode>10020020</towncode>
            <towncode01>I01</towncode01>
            <townname>西區</townname>
        </townItem>
</townItems>
```

六、代碼服務－地段清單

(一) URL

https://api.nlsc.gov.tw/other/ListLandSection

URI	HTTP

	Method
../{縣市代碼}/{鄉鎮市區代碼}	GET

(二) 傳入參數說明

編碼：UTF-8

輸入參數	預設值	說明
{縣市代碼}		必填，以英文 1 碼表示，由 A~Z 組成，例如：A=臺北市
{鄉鎮市區代碼}		必填，以英文 1 碼及數字 2 碼表示，前者為縣市代碼，例如：A01=臺北市松山區

(三) 回傳格式：application/xml

編碼：UTF-8

Parent Node	Node	Value
<sectItem>	<office>	地所代碼
	<officestr>	地所名稱
	<sectcode>	地段代碼
	<sectstr>	地段名稱

(四) 範例

Request
https://api.nlsc.gov.tw/other/ListLandSection/B/B07
Response
<sectItems> <sectItem> <office>BA</office> <officestr>中山</officestr> <sectcode>0001</sectcode> <sectstr>繼光段一小段</sectstr> </sectItem> <sectItem> <office>BA</office> <officestr>中山</officestr> <sectcode>0002</sectcode>

```
            <sectstr>繼光段二小段</sectstr>
        </sectItem>
        <sectItem>
            <office>BA</office>
            <officestr>中山</officestr>
            <sectcode>0003</sectcode>
            <sectstr>繼光段三小段</sectstr>
        </sectItem>
</sectItems>
```


七、代碼服務－村里清單

(一) URL

https://api.nlsc.gov.tw/other/ListVillage

URI	HTTP Method
../{縣市代碼}/{鄉鎮市區代碼}	GET

(一) 傳入參數說明

編碼：UTF-8

輸入參數	預設值	說明
{縣市代碼}		必填，以英文 1 碼表示，由 A~Z 組成，例如：A=臺北市
{鄉鎮市區代碼}		必填，以英文 1 碼及數字 2 碼表示，前者為縣市代碼，例如：A01=臺北市松山區

(二) 回傳格式：application/xml

編碼：UTF-8

Parent Node	Node	Value
< village>	< villageId>	村里代碼

	< villageName>	村里名稱

(三) 範例

Request
https://api.nlsc.gov.tw/other/ListVillage/B/B01
Response
<villages>   <village>   <villageId>6600100-001</villageId>   <villageName>繼光里</villageName>   </village>   <village>   <villageId>6600100-002</villageId>   <villageName>大墩里</villageName>   </village>   <village>   <villageId>6600100-003</villageId>   <villageName>綠川里</villageName>   </village>   <village>   <villageId>6600100-004</villageId>   <villageName>公園里</villageName>   </village> </villages>

八、代碼服務－村里圖形

(一) URL

https://api.nlsc.gov.tw/other/GetMapVillage/

URI	HTTP Method
/GetMapVillage/{縣市代碼}/{鄉鎮市區代碼}/{村里代碼}	GET
/GetMapVillage/{縣市代碼}/{鄉鎮市區代	GET

碼}/{村里代碼}/{坐標類別代碼}	

(二) 傳入參數說明

編碼：UTF-8

輸入參數	預設值	說明
{縣市代碼}		必填，以英文 1 碼表示，由 A~Z 組成，例如：A=臺北市
{地段代碼}		必填，地段代碼 4 碼。可填空值或 NULL
{村里代碼}		必填，戶役政資訊系統資料代碼 11 碼
{坐標類別代碼}	EPSG4326	EPSG4326 (WGS84) EPSG3825 (TWD97/TM2 Zone119(澎湖)) EPSG3826 (TWD97/TM2 Zone121(臺灣))

(三) 回傳格式：KML

編碼：UTF-8

參照 KML(Keyhole Markup Language)格式。

(四) 範例

Request
https://api.nlsc.gov.tw/other/GetMapVillage/B/B01/66000010005
Response
<Data name="VILLCODE">   <value>66000010005</value> </Data> <Data name="COUNTYNAME">

```
        <value>臺中市</value>
</Data>
<Data  name="TOWNNAME">
        <value>中區</value>
</Data>
<Data  name="VILLNAME">
        <value>光復里</value>
</Data>
<Data  name="VILLENG">
        <value>Guangfu  Vil.</value>
</Data>
<Data  name="COUNTYID">
        <value>B</value>
</Data>
```


九、查詢文教設施

(一) URL

https://api.nlsc.gov.tw/other/MarkBufferAnlys/

URI	HTTP Method
../edu/{X 坐標}/{Y 坐標}/{半徑範圍}	GET

(二) 傳入參數說明

編碼：UTF-8

輸入參數	預設值	說明
{X 坐標}		必填，查詢點的緯度坐標
{Y 坐標}		必填，查詢點的經度坐標
{半徑範圍}		必填，以公尺為單位

(三) 回傳格式：application/json

編碼：UTF-8

代碼	說明
type	向量圖資類型

lon	經度坐標
lat	緯度坐標
marktype	
id	流水邊 ID
name	設施名稱
sname	設施簡稱
addr	設施地址
tel	設施電話
distance	離查詢點距離

(四) 範例

Request
https://api.nlsc.gov.tw/other/MarkBufferAnlys/edu/120.634413/24.153282/100
Response


```
[
        {
           "type": "Point",
           "lon": 120.633761,
           "lat": 24.153531,
           "marktype": "9920104",
           "id": "B0000001639",
           "name": "台灣自來水公司人力資源處訓練所",
           "sname": "台水人力資源處訓練所",
           "addr": "",
           "tel": "",
           "distance": 72
        }
]
```


十、查詢醫療設施

(一) URL

https://api.nlsc.gov.tw/ other/MarkBufferAnlys/

URI	HTTP Method

../med/{X 坐標}/{Y 坐標}/{半徑範圍}	GET

(二) 傳入參數說明

編碼：UTF-8

輸入參數	預設值	說明
{X 坐標}		必填，查詢點的緯度坐標
{Y 坐標}		必填，查詢點的經度坐標
{半徑範圍}		必填，以公尺為單位

(三) 回傳格式：application/json

編碼：UTF-8

代碼	說明
type	向量圖資類型
lon	經度坐標
lat	緯度坐標
marktype	
id	流水邊 ID
name	設施名稱
sname	設施簡稱
addr	設施地址
tel	設施電話
distance	離查詢點距離

(四) 範例

Request
https://api.nlsc.gov.tw/other/MarkBufferAnlys/med/120.634413/24.153282/1000
Response
[{

```
            "type": "Point",
            "lon": 120.640083,
            "lat": 24.149276,
            "marktype": "9930101",
            "id": "B0000001845",
            "name": "林新醫療社團法人林新醫院",
            "sname": "林新醫院",
            "addr": "臺中市南屯區惠中路三段 36 號",
            "tel": "04-22586688",
            "distance": 727
        }
]
```


十一、查詢工商設施

(一) URL

https://api.nlsc.gov.tw /other/MarkBufferAnlys/

URI	HTTP Method
../ bus/{X 坐標}/{Y 坐標}/{半徑範圍}	GET

(二) 傳入參數說明

編碼：UTF-8

輸入參數	預設值	說明
{X 坐標}		必填，查詢點的緯度坐標
{Y 坐標}		必填，查詢點的經度坐標
{半徑範圍}		必填，以公尺為單位

(三) 回傳格式：application/json

編碼：UTF-8

代碼	說明
type	向量圖資類型

lon	經度坐標
lat	緯度坐標
id	流水邊 ID
name	設施名稱
sname	設施簡稱
addr	設施地址
tel	設施電話
distance	離查詢點距離

(四) 範例

Request
https://api.nlsc.gov.tw/other/MarkBufferAnlys/bus/120.634413/24.153282/70
Response

[
{
"type": "Point",
"lon": 120.635056,
"lat": 24.153267,
"id": "B9000054114",
"name": "象映快速沖印店",
"sname": "象映快速沖印店",
"addr": "黎明路二段 498 號一樓",
"tel": "",
"distance": 65
}
]

十二、查詢鄰避設施

(一) URL

https://api.nlsc.gov.tw /other/MarkBufferAnlys/

URI	HTTP Method

../dis/{X 坐標}/{Y 坐標}/{半徑範圍}	GET

(二) 傳入參數說明

編碼：UTF-8

輸入參數	預設值	說明
{X 坐標}		必填，查詢點的緯度坐標
{Y 坐標}		必填，查詢點的經度坐標
{半徑範圍}		必填，以公尺為單位

(三) 回傳格式：application/json

編碼：UTF-8

代碼	說明
type	向量圖資類型
lon	經度坐標
lat	緯度坐標
marktype	
id	流水邊 ID
name	設施名稱
sname	設施簡稱
addr	設施地址
tel	設施電話
distance	離查詢點距離

(四) 範例

Request
https://api.nlsc.gov.tw/other/MarkBufferAnlys/dis/120.634413/24.153282/1000
Response
[{

```
            "type": "Point",
            "lon": 120.630057,
            "lat": 24.146829,
            "marktype": "9960203",
            "id": "B0000001554",
            "name": "台灣中油加油站中村站",
            "sname": "中油中村站",
            "addr": "臺中市南屯區五權西路二段 1001 號",
            "tel": "04-23812919",
            "distance": 841
    }
]
```


十三、圖層圖資說明

(一) URL

https://api.nlsc.gov.tw/other/MapLayerInfo/

URI	HTTP Method
../{圖層代碼}	GET

(二) 傳入參數說明

編碼：UTF-8

輸入參數	預設值	說明
{圖層代碼}	空白	圖層代碼，空白表示顯示所有圖層說明

(三) 回傳格式：application/json

編碼：UTF-8

代碼	說明

layerCode	圖層代碼
layerDate	建立日期
layerInfo	圖層說明
layerName	圖層名稱
layerSupply	圖資提供單位

(四) 範例

Request
https://api.nlsc.gov.tw/other/MapLayerInfo/nURBAN
Response

[
{
"layerCode": "nURBAN",
"layerDate": "108 年 8 月",
"layerInfo": "本中心依據內政部營建署城鄉發展分署授權資料產製...",
"layerName": "非都市土地使用分區圖",
"layerSupply": "內政部營建署城鄉發展分署"
}
]

十四、交叉路口-縣市鄉鎮市區查詢主要道路

(一) URL

https://api.nlsc.gov.tw/idc/ListRoadM/

URI	HTTP Method
../{縣市代碼}/{鄉鎮市區代碼}	GET

(二) 傳入參數說明

編碼：UTF-8

輸入參數	預設值	說明

{縣市代碼}		必填，以英文 1 碼表示，由 A~Z 組成，例如：A=臺北市
{鄉鎮市區代碼}		必填，以英文 1 碼及數字 2 碼表示，前者為縣市代碼，例如：A01=臺北市松山區

(三) 回傳格式：application/xml

編碼：UTF-8

Parent Node	Node	Value
<roads> <road>	<name>	主要道路名稱

(四) 範例

Request
https://api.nlsc.gov.tw/idc/ListRoadM/B/B01
Response
<roads> <road> <name>八德街</name> </road> <road> <name>三民路一段</name> </road> </roads>

十五、交叉路口-縣市道路關鍵字查詢主要道路

(一) URL

https://api.nlsc.gov.tw/idc/TextQueryRoad/

URI	HTTP Method
../{縣市代碼}/{道路關鍵字}	GET

(二) 傳入參數說明

編碼：UTF-8

輸入參數	預設值	說明
{縣市代碼}		必填，以英文 1 碼表示，由 A~Z 組成，例如：A=臺北市
{道路關鍵字}		必填，輸入上述縣市之道路關鍵字

(三) 回傳格式：application/xml

編碼：UTF-8

Parent Node	Node	Value
<roads> <road>	<name>	主要道路名稱
	<townCode>	鄉鎮市區代碼（地政）
	<townname>	鄉鎮市區名稱

(四) 範例

Request
https://api.nlsc.gov.tw/idc/TextQueryRoad/B/大業
Response
<roads> <road> <name>大業路</name> <townCode>B04</townCode> <townName>西區</townName> </road> <road> <name>大業路</name> <townCode>B14</townCode> <townName>梧棲區</townName> </road> </roads>

十六、交叉路口-縣市鄉鎮市區路名查詢交叉路口

(一) URL

https://api.nlsc.gov.tw/idc/ListRoadCross/

URI	HTTP Method
../{縣市代碼}/{鄉鎮市區代碼}/{道路關鍵字}	GET

(二) 傳入參數說明

編碼：UTF-8

輸入參數	預設值	說明
{縣市代碼}		必填，以英文 1 碼表示，由 A~Z 組成，例如：A=臺北市
{鄉鎮市區代碼}		以英文 1 碼及數字 2 碼表示，前者為縣市代碼，例如：A01=臺北市松山區
{道路關鍵字}		必填，輸入上述縣市之道路關鍵字

(三) 回傳格式：application/xml

編碼：UTF-8

Parent Node	Node	Value
<crossRoads> <crossRoad>	<name>	主要道路名稱
	<X>	經度坐標
	<Y>	緯度坐標

(四) 範例

Request
https://api.nlsc.gov.tw/idc/TextQueryRoad/B/B04/大業路
Response
<crossRoads>   <crossRoad>   <name>大業北路</name>   <x>120.65421485970609</x>   <y>24.153577918610775</y>   </crossRoad>   <crossRoad>   <name>東興路三段</name>   <x>120.65300444741386</x>   <y>24.153593228777833</y>   </crossRoad> </crossRoads>

十七、指定坐標回傳國土利用現況調查成果圖的屬性

(一) URL

https://api.nlsc.gov.tw/other/LandUsePointQuery/

URI	HTTP Method
. LandUsePointQuery/{ X 坐標}/{ Y 坐標}	GET
. LandUsePointQuery/{ X 坐標}/{ Y 坐標}/{坐標類別代碼}	GET

(二) 傳入參數說明

編碼：UTF-8

輸入參數	預設值	說明
{X 坐標}		查詢點的 X 坐標
{Y 坐標}		查詢點的 Y 坐標
{坐標類別代碼}	EPSG4326	EPSG4326 (WGS84)

		EPSG3826 (TWD97/TM2 Zone121(臺灣))

(三) 回傳格式：application/xml

編碼：UTF-8

Parent Node	Node	Value
<crossRoads> <crossRoad>	<YEAR>	圖磚年份
	<LYEAR>	調查年月
	<LMONTH>	緯度坐標
	<Lcode_C1>	一級分類代碼
	<Lname_C1>	一級分類說明
	<Lcode_C2>	二級分類代碼
	<Lname_C2>	二級分類說明
	<Lcode_C3>	三級分類代碼
	<LCODE>	最高分級代碼
	<NAME>	最高分級中文說明

(四) 範例

Request
https://api.nlsc.gov.tw/other/LandUsePointQuery/120.634413/24.153282/4326
Response
<root> <ITEM> <YEAR>108</YEAR> <LYEAR>2019</LYEAR> <LMONTH>108</LMONTH> <Lcode_C1>11</Lcode_C1> <Lname_C1>公共利用土地</Lname_C1> <Lcode_C2>0601</Lcode_C2> <Lname_C2>政府機關</Lname_C2>

```
        <Lcode_C3>060100</Lcode_C3>
        <LCODE>060100</LCODE>
        <NAME>政府機關</NAME>
    </ITEM>
```


第七節 圖臺 API 服務

一、設定進入圖臺的顯示層級及坐標

(一) URL

https://maps.nlsc.gov.tw/go/

URI	HTTP Method
../{經度}/{緯度}	GET
../{經度}/{緯度}/{顯示層級}	GET
../{經度}/{緯度}/{顯示層級}/{底圖設定}/	GET
../{經度}/{緯度}/{顯示層級}/{底圖設定}/{額外圖層}	GET

(二) 傳入參數說明

編碼：UTF-8

輸入參數	預設值	說明
{經度}		必填，WGS84 經度
{緯度}		必填，WGS84 緯度
{顯示層級}		填寫數字，層級區間為 6~20
{底圖設定}		底圖圖層代碼 (需加_B)
{額外圖層}		圖層代碼，多筆以透點隔開

(三) 範例

Request
https://maps.nlsc.gov.tw/go/120.64771/24.12957/15/EMAP_B/DMAPS,ROAD
Response

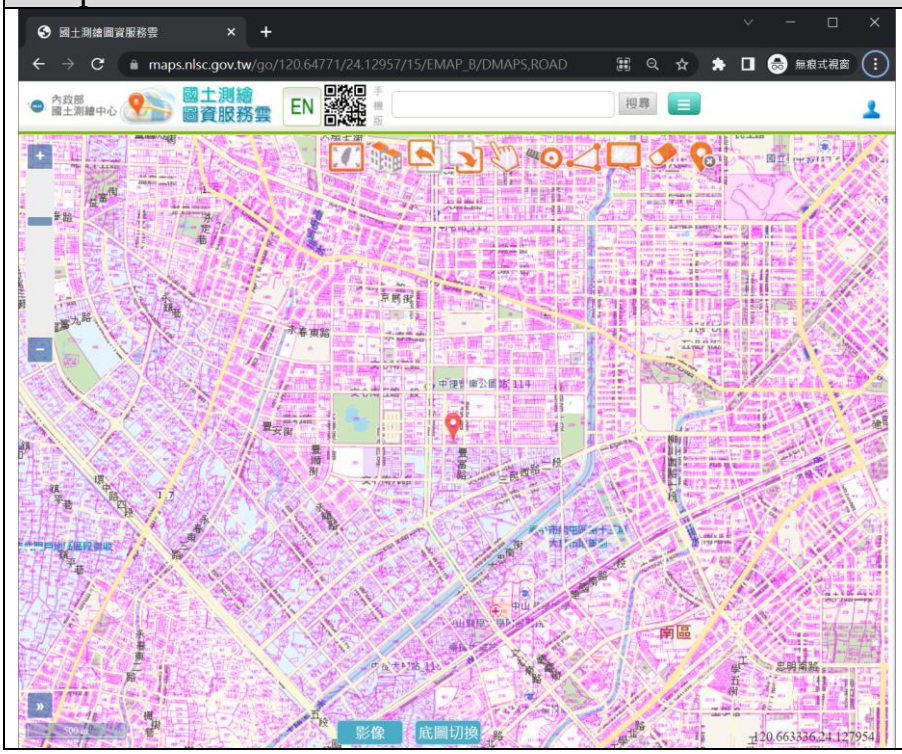

二、設定進入圖臺的底圖及額外圖層

(一) URL

https://maps.nlsc.gov.tw/open/

URI	HTTP Method
../{底圖設定}	GET
../{底圖設定}/{額外圖層}	GET

(二) 傳入參數說明

編碼：UTF-8

輸入參數	預設值	說明

{底圖設定}		底圖圖層代碼(需加_B)
{額外圖層}		圖層代碼，多筆以透點隔開

(三) 範例

Request
https://maps.nlsc.gov.tw/open/EMAP_B/fireplug,DMAPS
Response

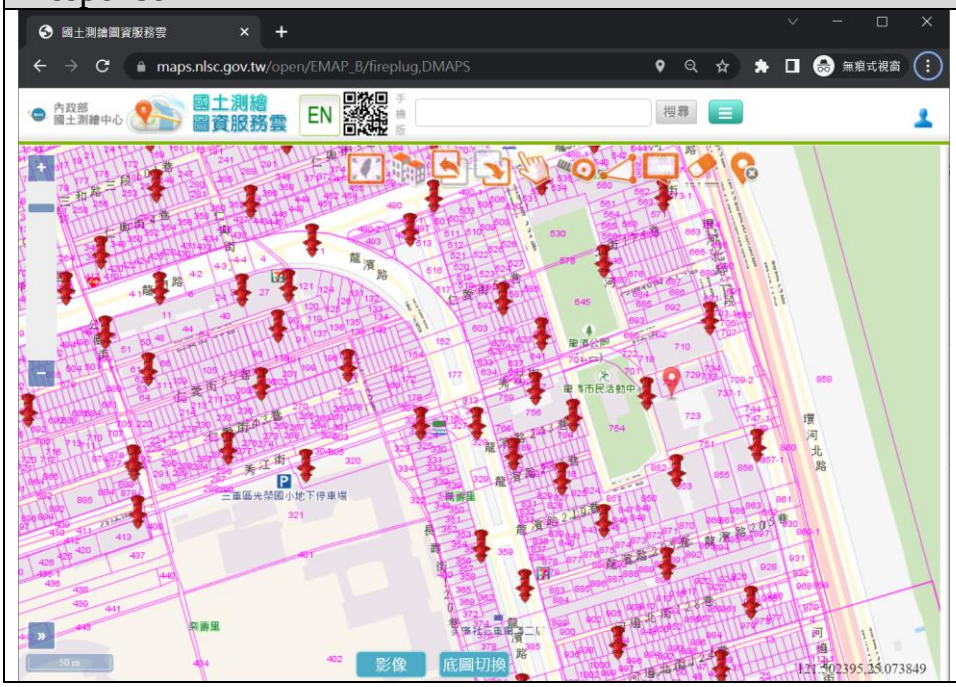

三、設定圖資服務雲的使用語系

(一) URL

https://maps.nlsc.gov.tw/

URI	HTTP Method
../{語言版本}	GET
../{語言版本}/{進入點}	GET

(二) 傳入參數說明

編碼：UTF-8

輸入參數	預設值	說明
{語言版本}		EN=英文、ZH=中文
{進入點}	空白	MAP=圖臺、空白=首頁

(三) 範例

Request
https://maps.nlsc.gov.tw/EN/MAP
Response

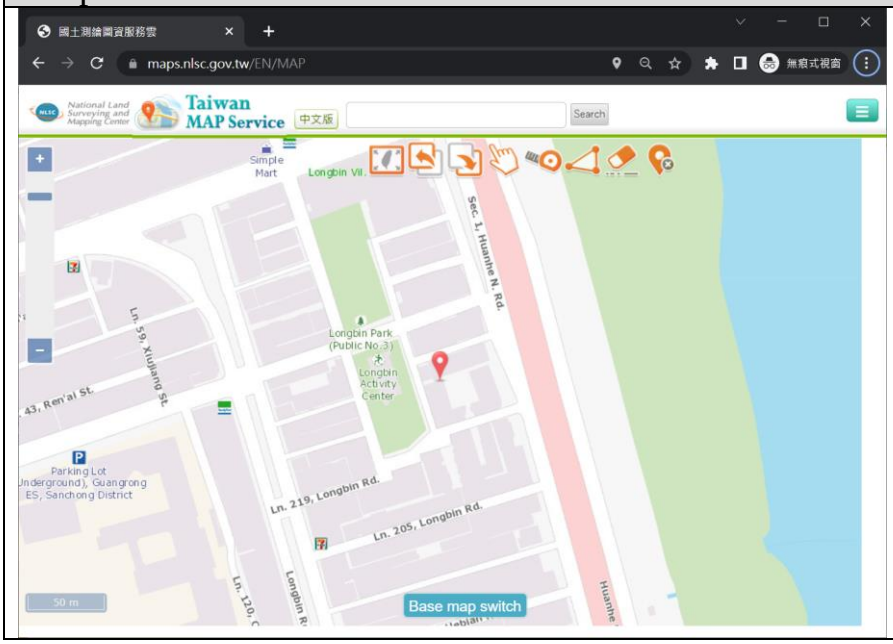

四、設定進入圖臺是否顯示離線地圖功能

(一) URL

https://maps.nlsc.gov.tw/ZH/OMMAP

(二) 範例

Request
https://maps.nlsc.gov.tw/ZH/OMMAP
Response

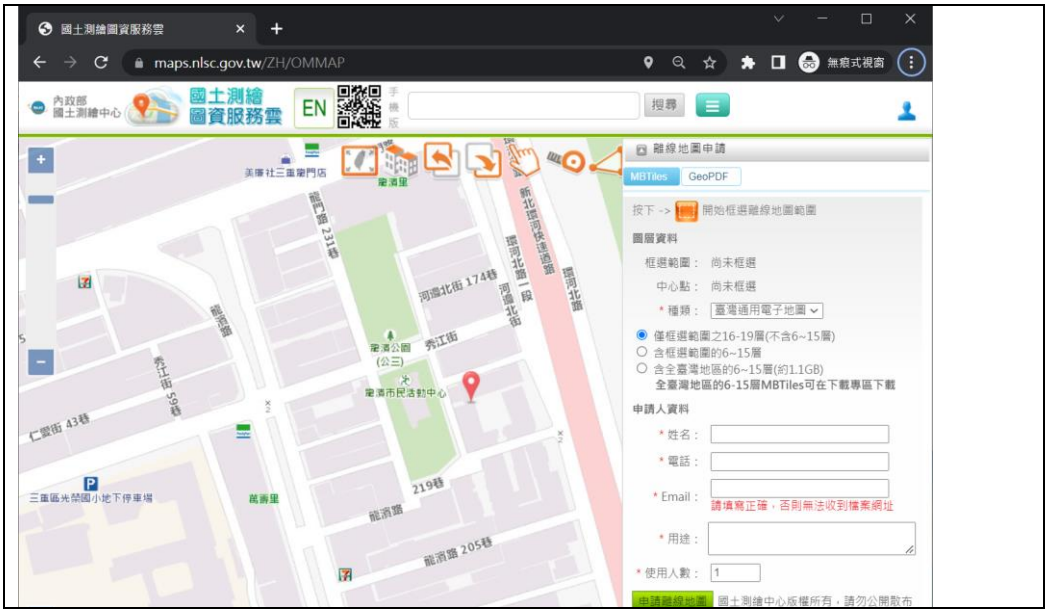

五、設定進入圖臺的地號並著色

(一) URL

https://maps.nlsc.gov.tw/goland/

URI	HTTP Method
../{縣市代碼}/{地段及地號}	GET
../{縣市代碼}/{地段及地號}/{底圖設定}	GET
../{縣市代碼}/{地段及地號}/{底圖設定}/{額外圖層}	GET

(二) 傳入參數說明

編碼：UTF-8

輸入參數	預設值	說明
{縣市代碼}		必填，以英文 1 碼表示，由 A~Z 組成，例如：A=臺北市
{地段及地號}		必填，地段數字 4 碼及地號數字 8 碼，多筆可以逗點隔開

{底圖設定}		底圖圖層代碼 (需加_B)
{額外圖層}		圖層代碼，多筆以透點隔開

(三) 範例

Request
https://maps.nlsc.gov.tw/goland/B/201303420000,201303410000
Response

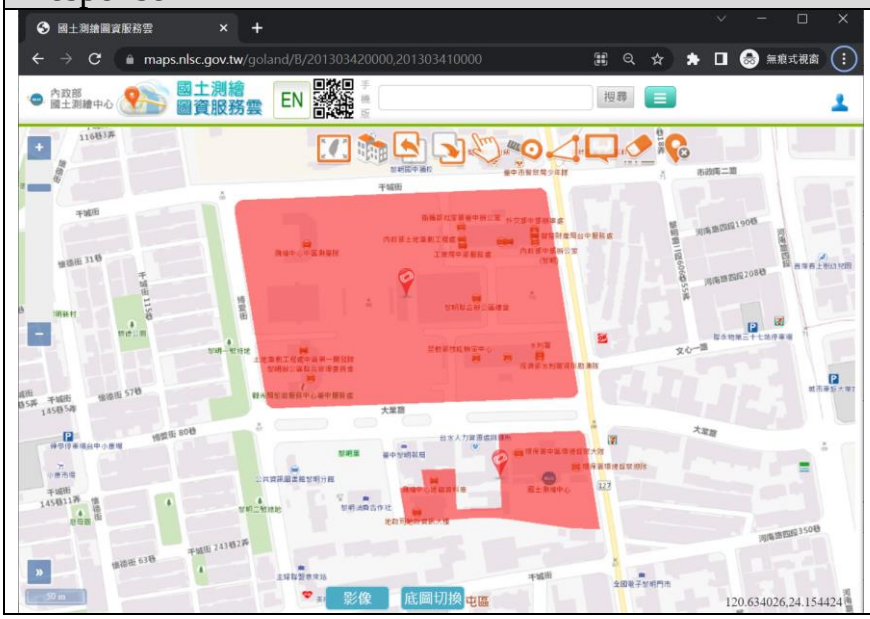

六、設定進入圖臺的路徑規劃點

(一) URL

https://maps.nlsc.gov.tw/maps/route/

URI	HTTP Method
../{終點(WGS84)}/	GET
../{起點(WGS84)}/{終點(WGS84)}/	GET

(二) 傳入參數說明

編碼：UTF-8

輸入參數	預設值	說明
{起點(WGS84)}		經緯度{X 坐標,Y 坐標}
{終點(WGS84)}		經緯度{X 坐標,Y 坐標}

(三) 範例
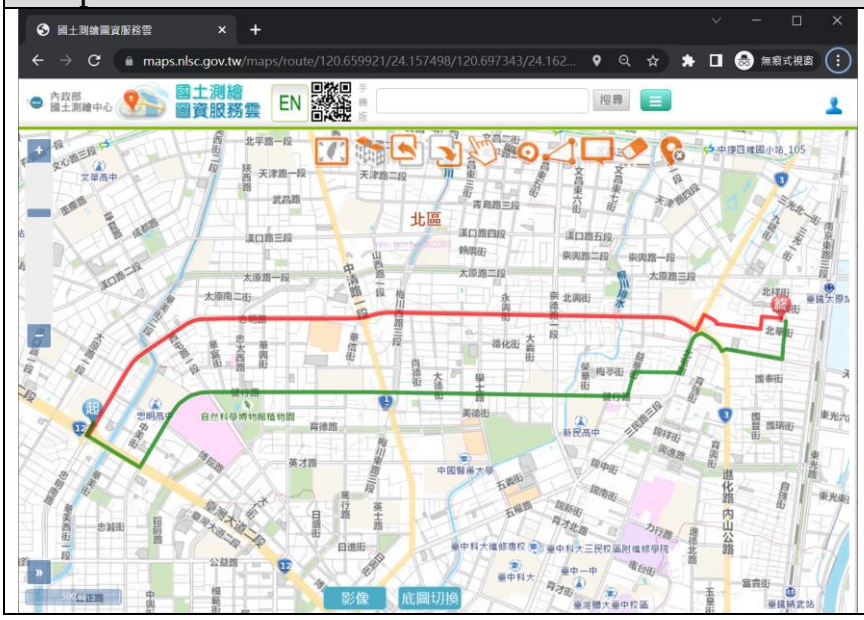
Request
https://maps.nlsc.gov.tw/maps/route/120.659921/24.157498/120.697343/24.162667
Response